

ver a cidade
Florianópolis

RELATÓRIO ANUAL
INDICADORES 2025
FLORIANÓPOLIS

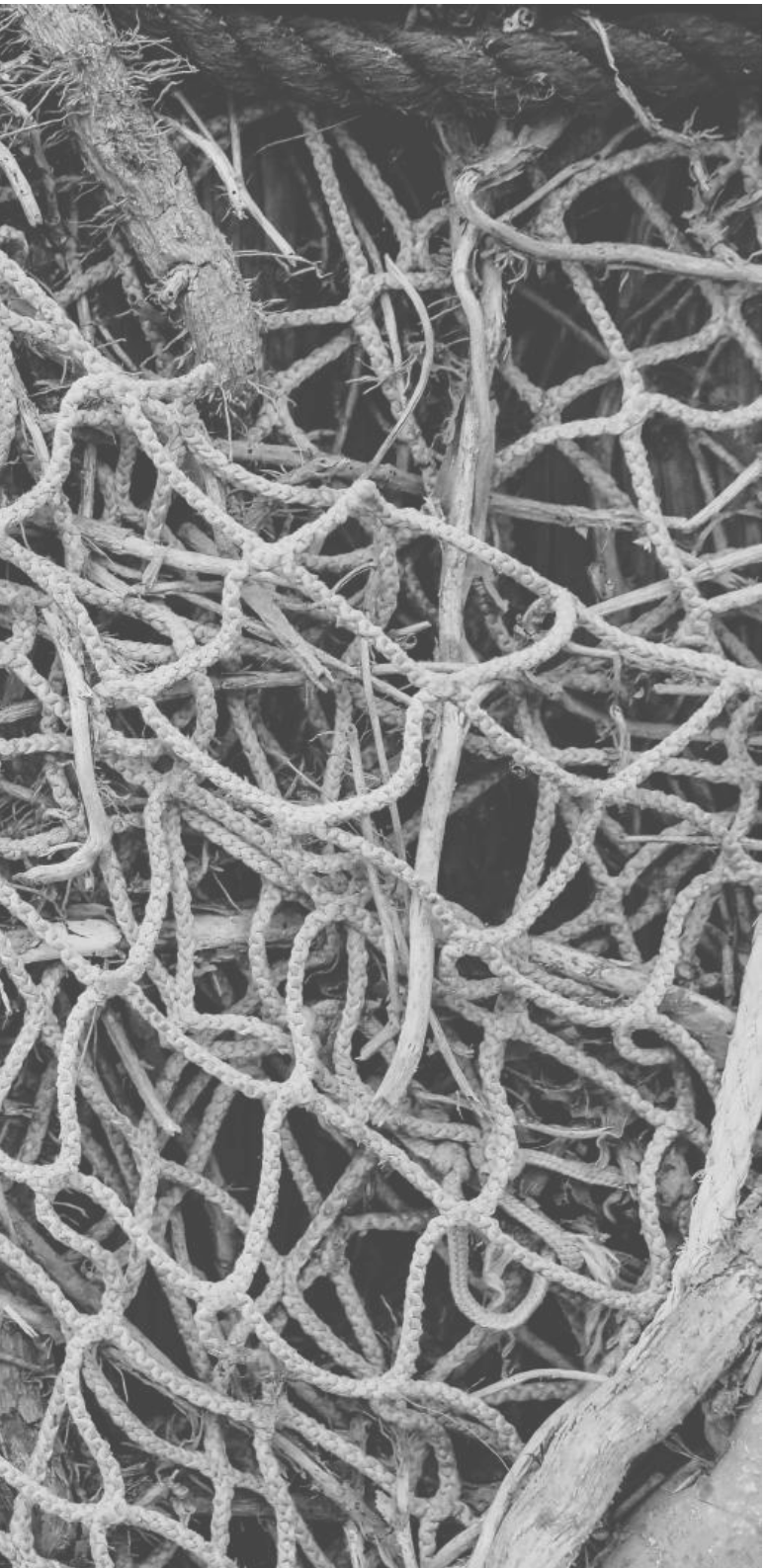

ver a cidade
Florianópolis

RELATÓRIO DOS INDICADORES

FLORIANÓPOLIS

2025

1. APRESENTAÇÃO

O 9º º Relatório Anual de Progresso dos Indicadores de Florianópolis (RAPI) é o resultado da coleta e análise de indicadores de sustentabilidade ambiental, urbana e fiscal, bem como um conjunto de recomendações aos entes públicos.
O documento dá visibilidade a um conjunto de 205 indicadores, e se baseia na metodologia do Programa Cidades Emergentes e Sustentáveis (CES), do Banco Interamericano de Desenvolvimento (BID).
Esse trabalho coletivo envolve, desde 2017, diferentes organizações tem como objetivo acompanhar, de forma técnica e imparcial, o desenvolvimento da cidade em questões que impactam a sua sustentabilidade e a qualidade de vida de seus cidadãos
O Grupo de Trabalho que coordena a coleta, semaforização e elaboração do relatório final do RAPI é composto pela Associação FloripAmanhã, a Universidade Federal de Santa Catarina (UFSC) e o Observatório Social do Brasil – Florianópolis.

2. CONTEXTO

O RAPI apresenta-se como importante ferramenta para que o poder público, as entidades da sociedade civil e os cidadãos em geral avaliem as questões urbanas a partir do real conhecimento de dados confiáveis e atualizados.
Além disso, à medida em que o cidadão se apropria de informações confiáveis sobre seu território, o debate político se torna mais rico, mais participativo e com melhores resultados para toda a população.

3. OBJETIVO:

O objetivo geral do Relatório Anual de Análise de Progresso dos Indicadores (RAPI) de Florianópolis é auxiliar o governo e a sociedade a estabelecerem e seguirem prioridades com metas claras e mensuráveis, para o desenvolvimento sustentável da cidade, e contribuir para a avaliação das políticas públicas urbanas, a partir de uma visão técnica, objetiva e metodologicamente embasada.
Para alcançar esses objetivos, este documento traz não somente os indicadores em si, mas também recomendações aos entes públicos para que estes possam aprimorar suas políticas públicas, de forma a viabilizar o atingimento de melhores níveis de desenvolvimento sustentável.
Em nosso 9º exercício de monitoramento, trazemos a público um “raio-x” de temas como mobilidade, saneamento básico, saúde, educação, segurança, uso adequado do solo, entre outros que influenciam diretamente na qualidade de vida de quem escolheu viver em Florianópolis.

4. ESTRUTURA DO RAPI 2024-2025

A seguir detalhamos os pilares e seus respectivos temas, com a quantidade de indicadores por tema:

4.1. Dimensão Ambiental: 3 Pilares e 8 Temas – 32 indicadores

4.1.1. Pilar - Manejo Ambiental e Consumo de Recursos Naturais – 23 indicadores

4.1.1.1. Tema – Água – 06 indicadores

4.1.1.2. Tema - Saneamento e Drenagem – 03 indicadores

4.1.1.3. Tema - Gestão de Resíduos Sólidos – 08 indicadores

4.1.1.4. Tema – Energia – 06 indicadores

4.1.2. Pilar – Mitigação dos Gases de Efeito Estufa e Outras Formas de Contaminação – 04 indicadores

4.1.2.1. Tema - Qualidade do ar – 02 indicadores

4.1.2.2. Tema - Mitigação de Mudanças climáticas – 01 indicadores

4.1.2.3. Tema – Ruído – 01 indicador

4.1.3. Pilar – Redução da Vulnerabilidade Diante de Desastres Naturais e Adaptação à Mudança do Clima – 05 indicadores

4.1.3.1. Tema – Vulnerabilidade Frente a Desastre Naturais No Contexto da Mudança de Clima – 05 indicadores

4.2. Dimensão Urbana: 5 Pilares e 11 Temas – 142 indicadores

4.2.1. Pilar - Controle do Crescimento e Melhoria do Habitat Urbano – 18 indicadores

4.2.1.1. Tema - Uso do Solo e Ordenamento Territorial – 11 indicadores

4.2.1.2. Tema - Desigualdade Urbana – 07 indicadores

4.2.2. Pilar – Promoção do Transporte Urbano Sustentável – 23 indicadores

4.2.2.1. Tema - Mobilidade e Transporte – 23 indicadores

4.2.3. Pilar – Promoção do Desenvolvimento Econômico Local Competitivo Sustentável – 12 indicadores

4.2.3.1. Tema - Ambientes de Negócios – 01 indicadores

4.2.3.2. Tema - Tecido Produtivo – 08 indicadores

4.2.3.3. Tema - Mercado Laboral – 03 indicadores

4.2.3.4.

4.2.4. Pilar – Oferta de Serviços Sociais de Alto Nível e Promoção da Coesão Social – 72 indicadores

4.2.4.1. Tema - Educação – 19 indicadores

4.2.4.2. Tema - Segurança – 10 indicadores

4.2.4.3. Tema - Saúde – 43 indicadores

4.2.5. Competitividade – 17 indicadores

4.2.5.1. Tema - Capital Humano – 02 indicadores

4.2.5.2. Tema - Tecido Empresarial – 15 indicadores

4.3. Dimensão Fiscal: 04 Pilares – 06 Temas – 31 indicadores

4.3.1. Mecanismos Adequados de Governo – 11 indicadores

4.3.1.1. Tema - Gestão Pública Participativa – 01 indicadores

4.3.1.2. Tema - Gestão Pública Moderna – 09 indicadores

4.3.1.3. Tema - Transparência – 01 indicadores

4.3.2. Gestão Adequada da Receita – 11 indicadores

4.3.2.1. Tema - Impostos e Autonomia Financeira – 11 indicadores

4.3.3. Gestão Adequada da Despesa – 05 indicadores

4.3.3.1. Tema - Gestão do Gasto Público – 05 indicadores

4.3.4. Gestão Adequada da Dívida – 04 indicadores

4.3.4.1. Tema - Dívida – 04 indicadores

5. SEMAFORIZAÇÃO DOS INDICADORES

O Relatório RAPI 2024-2025 está dividido em 03 dimensões: **sustentabilidade ambiental e mudança de clima** (32 indicadores), **sustentabilidade urbana** (142 indicadores) e **sustentabilidade fiscal e governança** (31 indicadores). Essas dimensões são subdivididas em 12 pilares e 25 temas, compondo um conjunto de 205 indicadores.

Numa visão geral os indicadores foram semaforizados da seguinte forma:

a) **"Verde"** – **40** indicadores – Indicadores que a cidade atingiu resultados satisfatórios;
b) **"Amarelo"** – **34** indicadores – indicadores que a cidade revela níveis que ainda requerem atenção.
c) **" Vermelho"** – **26** indicadores – indicadores que a cidade está abaixo do nível satisfatório e requerem atenção especial.
d) **"Cinza" – 36** indicadores que a fonte de dados não acompanha, ou não informou, ou foram informados fora dos parâmetros solicitados
e) **"Azul"** - **69** indicadores novos não semaforizados.

5.1 GRÁFICO COMPARATIVO DA SEMAFORIZAÇÃO DOS ÚLTIMOS 6 ANOS

			2024	2023	2022	2021	2020
TOTALIZADORES	Indicadores novos não semaforizados.	AZUL	69	75	72	56	62
	indicadores que a administração não acompanha, ou não informou, ou foram informados fora dos parâmetros solicitados	CINZA	36	21	17	42	39
	Indicadores que a cidade atingiu resultados satisfatórios	VERDE	40	40	40	38	36
	Indicadores que a cidade atingiu níveis que ainda requerem atenção	AMARELO	34	37	23	19	17
	Indicadores que a cidade está abaixo do nível satisfatório e requerem atenção especial	VERMELHO	26	29	31	28	29
	quantidade total de indicadores		**205**	**202**	**183**	**183**	**183**

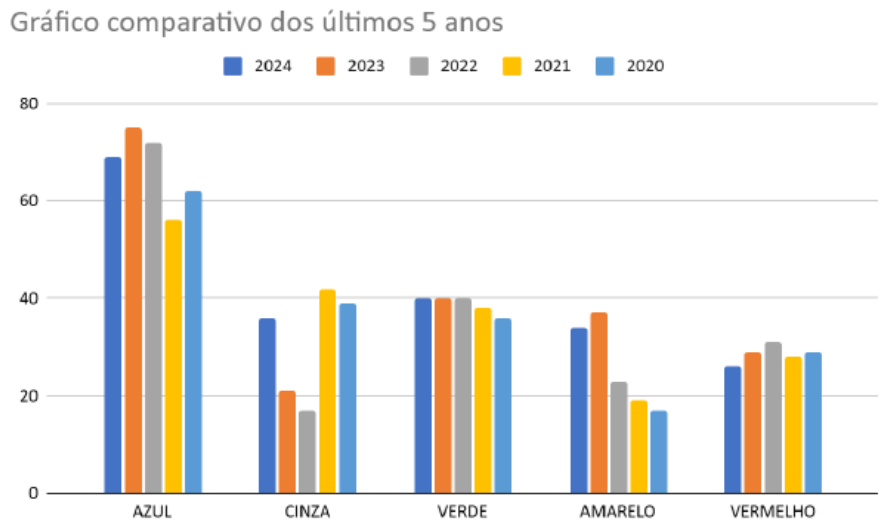

6. TABELA DOS INDICADORES DE SUSTENTABILIDADE:

dimensões	PILAR	TEMA	SUBTEMA		ORDEM CES	NOVA ORDE	ORDEM FLORIP	ÓRGÃO RESPONSÁVEL	INDICADOR	FAIXAS PARA SEMAFORIZAÇÃO			2019	2020	2021	2022	2023	2024
		ÁGUA	COBERTURA DE ÁGUA	1	1	1	7.1.1	CASAN/FNR	Porcentagem de pessoas com serviço de abastecimento de água potável em relação à população total do município	> 90%–100%	75%–90%	< 75%	100%	100%	**100%**	**100%**	100%	93%
			EFICIÊNCIA NO USO DA ÁGUA	2	2	2	7.1.5	CASAN/FNR	Quantidade total do consumo de água em litros por dia dividida pelo total da população. Inclui uso não doméstico.	120–200	80–120 ou 200–250	< 80 ou > 250	173,5 l/pessoa/dia	172,9 l/pessoa/dia	**0,1631 m3/pessoa/dia = 163,1 l/pessoa/dia**	**0,1726 m³pessoa/dia = 172,6 l/pessoa/dia**	0,1799 = 179,9 l/pessoa/dia	178,9 L/pessoa/dia
			EFICIÊNCIA NO SERVIÇO DE ABASTECIMENTO DE ÁGUA	3	3	3		CASAN	Média anual de horas/dia em que há o fornecimento contínuo de água.	> 20 h/dia	12–20 h/dia	< 12 h/dia	24h	23,86 horas/dia	**23,86 horas/dia**	**23,98 horas/dia**	24,00 horas/dia	24,00 horas/dia
				4	4	4	7.1.4	CASAN/FNR	Qualidade da água: Porcentagem do número total de testes conformes em relação ao número total de testes de qualidade de água tratada realizados.	> 97%	90%–97%	< 90%	98,53%	95,19%	**95,87%**	**97,20%**	97%	96,08%
				5	5	5	7.1.6	CASAN/FNR	Água não contabilizada = Índice de perdas na distribuição de água.	0%–30%	30%–45%	> 45%	42,41%	43,84%	**43,80%**	**39,30%**	35,87%	38,09%
				6	6	6		SDE/SEMA	Número remanescente de anos de saldo hídrico positivo (volume de água disponível dividido pelo consumo anual real (faturado + perdido).	> 10	5–10	< 5	ND	ND	**85%**	ND	ND	ND
		SANEAMENTO E DRENAGEM	COBERTURA DE SANEAMENTO	7	7	7		CASAN	Porcentagem de moradias com ligação ao sistema de esgoto	> 75%	75%–60%	< 60%	66,9% da cobertura urbana em Florianópolis	67,42%	**68,89% da cobertura urbana em Florianopolis * das areas atendidas pela Casan**	**68,39% da cobertura urbana em Florianópolis**	66,67%	64,81%
			TRATAMENTO DE ÁGUA RESIDUÁRIAS	8	8	8		CASAN	Porcentagem de águas residuais ou efluente (águas de esgoto) tratadas: total de m³ de águas residuais que entram anualmente nas estações de tratamento dividido pelo total de m³ de água faturadas.	> 60%	40%–60%	< 40%	58,58%	55,56%	**65,07%**	**62,69%**	60,14%	63,15%
			EFETIVIDADE DA DRENAGEM	9	9	9		SMSP	Porcentagem anual de moradias afetadas por inundações intensas decorrentes de transbordamentos dos sistemas de drenagem e esgoto e de inundações causadas por rios e marés.	< 0,5%	0,5–3	> 3%	0,50%	**7,00%**	**9,00%**	**11,00%**	**13%**	15%
			A COLETA DE RESÍDUOS SÓLIDOS	10	10	10		COMCAP	Porcentagem das moradias com coleta regular de resíduos sólidos.	90%–100%	80%–90%	< 80%	100%	100%	**100%**	**100%**	100%	100
			VOLUME DE RESIDUOS SÓLIDOS	11	L 5	11		COMCAP	Toneladas totais de resíduos sólidos recolhidos (lixo convencional, coleta seletiva, lixo hospitalar, lixo pesado).	Sem valor de referência			212.303 ton	205.291 ton	**198.945,33**	**227.444,05**	253.577,01	259.313,04
				12	**NOVO**	12		COMCAP	Quantidade (kg) de resíduos sólidos coletados por habitante, por dia (população projetada IBGE)	≤ 1,0	1,01 - 1,5	>1,5	1,16 kg/hab/dia (pop 500.973)	1,10 kg	**1,05 kg/hab/dia**	**1,09**	1,28 kg/hab/dia	1,14

dimensões	PILAR	TEMA	SUBTEMA		ORDEM CES	NOVA ORDE	ORDEM FLORIP	ÓRGÃO RESPONSÁVEL	INDICADOR	FAIXAS PARA SEMAFORIZAÇÃO			2019	2020	2021	2022	2023	2024
	MANEJO AMBIENTAL E CONSUMO DOS RECURSOS NATURAIS	GESTÃO DE RESÍDUOS SÓLIDOS	DISPOSIÇÃO FINAL DOS RESÍDUOS SÓLIDOS	13	11	13	7.3.5	COMCAP/FNR	Porcentagem de resíduos sólidos municipais depositados em aterros sanitários	<35%	36%-50%	> 50%	92,85%	ND	**93,27%**	**88,82%**	86,38%	86,81
				14	12	14		COMCAP	Vida remanescente útil das instalações de aterro sanitário	> 8	5–8	< 5	ND	Não dispomos deste informação. O Aterro Sanitário, é operado por empresa privada que também recebe resíduos de outros municípios	**16 anos(2020), sem contar com área a ser ampliada.**	**ND**	**ND**	**24**
			TRATAMENTO DOS RESÍDUOS SÓLIDOS	15	14	15		COMCAP	Porcentagem de resíduos sólidos municipais compostados pela Prefeitura	> 20%	5%–20%	< 5%	1,93%	2,30%	**0,91%**	**3,58%**	4,56%	12,93
				16	15	16	7.3.4	COMCAP/FNR	Porcentagem de resíduos sólidos separados e classificados para reciclagem	> 25%	15%–25%	< 15%	5,22%	5,90%	**3,76%**	**7,60%**	9,05%	10,73
				17	16	17	7.3.6	COMCAP/FNR	Porcentagem de resíduos sólidos tratados em usinas de geração de energia a partir de resíduos em relação ao total de resíduos sólidos produzidos.	> 20 %	10%-19%	< 10%	0%	0%	**0%**	**0%**	0%	0%
			COBERTURA ENERGÉTICA	18	17	18		CELESC	Porcentagem de domicílios(residenciais) com ligação autorizada à energia elétrica	90%–100%	70%–90%	< 70%	Não temos informação do número de ligações clandestinas.	224.611 unidades consumidoras residencias	264.673 unidades consumidoras	271.230 número total de unidades consumidoras	276.889 em dez de 2023 - 99,93% (Base utilizando o CENSO 2022 do IBGE).	98,08%
				19		19	7.4.6	SC GÁS/FNR	Número de conexões de serviço de distribuição de gás - residencial (por 100 mil habitantes)	> 54.000	> 33.000 = < 54.000	< 33.000		2.585 unidades residenciais = 508,03/100 mil	**2.612 unidades residenciais = 516,2/100 mil**	3.506 unidades residenciais = 652,87/100 mil	3.740 unidades residenciais = 649,31/100 mil	4.588 unidades residenciais = 796,53/100 mil
				20	19	20	7.4.7	CELESC/FNR	Média de interrupção do fornecimento de energia elétrica por domicílio/ano, expresso em h/domicílio/ano	< 7h	7–10h	> 10h	5,42 vezes (ano)	4,46 (vezes ano)	**7,24**	**CELESC = 5,77 h/domicílio/ano**	5,45 h/domicílio/ano (2023)	5,61 h/domicílio/ano

dimensões	PILAR	TEMA	SUBTEMA		ORDEM CES	NOVA ORDE	ORDEM FLORIP	ÓRGÃO RESPONSÁVEL	INDICADOR	FAIXAS PARA SEMAFORIZAÇÃO			2019	2020	2021	2022	2023	2024
AMBIENTAL		ENERGIA	EFICIÊNCIA ENERGÉTICA	21	21	21		CELESC	Consumo anual de eletricidade por cliente residencial em Kw/h	1500–3500 kWh/por domicílio/ano	900–1500 kWh/por domicílio/ano 3500–5000 kWh/por domicílio/ano	< 900 kWh/por domicílio/ano > 5000 kWh/por domicílio/ano	2.536,56 kWh/ano	2.885,36 kWh/ano	**2.877,59**	**2.975,27**	**3.071,78**	3.286,75
				22	**NOVO**	22		COSIP	Porcentagem da iluminação pública que utiliza a tecnologia LED	> 50%	50% - 30%	< 30%	13,2% de unidades LED instaladas no parque de IP (7.410 unidades LED de um total de 55.994 unidades).	15,80%	**17,50%**	**17,5% 10.913 Luminárias**	45% 25.927 luminárias	77% - 44.660 luminárias
			ENERGIA ALTERNATIVA E RENOVÁVEL	23		23	7.4.4	CELESC /FNR	Energia proveniente de fontes renováveis (porcentagem)	> 50%	20%–50 %	< 20%		0,63%	**26,70%**	**1,95%**	**1,95% (2022)**	3,88%
		QUALIDADE DO AR	CONTROLE DA QUALIDADE DO AR E CONCENTRAÇÃO DE CONTAMINANTES NO AR	24	26	24		FLORAM	Índice de qualidade do ar	0–50	51–100	> 100	Não informado	ND	**ND**	**ND**	ND	ND
				25	27	25	6.4.2	FLORAM/FNR	Concentração de Material Particulado (MP) 10	< 50 MP 10 em média em 24 horas em µg/m3	50–150 MP 10 em média em 24 horas em µg/m3	> 150 MP 10 em média em 24 horas em µg/m3	Não informado	ND	**ND**	**ND**	ND	ND
		MITIGAÇÃO DA MUDANÇA CLIMÁTICA	EMISSÕES TOTAIS DE GEE	26	29	26	6.3.3	FLORAM/FNR	Emissões de GEE -Toneladas per capita (População projetada do IBGE)	< 5	5–10	> 10	2,17	ND	**ND**	**ND**	1,7412 toneladas metricas de CO2e per capita "	ND

dimensões	PILAR	TEMA	SUBTEMA		ORDEM CES	NOVA ORDE	ORDEM FLORIP	ÓRGÃO RESPONSÁVEL	INDICADOR	FAIXAS PARA SEMAFORIZAÇÃO			2019	2020	2021	2022	2023	2024
	MITIGAÇÃO DOS GASES DE EFEITO ESTUFA E OUTRAS FORMAS DE CONTAMINAÇÃO	Ruido	CONTROLE DE RUIDOS	27	NOVO	27		FLORAM	Média anual (em decibéis) de ruído nos 5 principais pontos críticos da cidade	< 70 decibéis	70 - 80 decibéis	> 80 decibéis	Trata-se de uma métrica que o Departamento não acompanha. A métrica que podemos disponbilizar são os bairros com maior percentual de denúncias: Centro 22,8%; Canasvieiras 7,1%, Ingleses 6,8%, Córrego Grande 4,4%, Capoeiras 4,4%, Estreito 3,7%, Saco dos limões 3,7%, do total de 353 denúncias recebidas no Departamento no ano de 2019.	Trata-se de uma métrica que o Departamento ainda não consegue acompanhar. A métrica possível é por bairros com maior percentual de denúncias do total de 278 denúncias recebidas no Departamento no ano de 2020: Centro - 24,90%, Campeche - 9,64%, Coqueiros - 9,04%, Canasvieiras - 7,83%, Estreito - 7,23%, Ingleses - 6,63%, Itacorubi - 5,63%, Corrego grande - 5,42%, Morro as pedras - 4,82%, Trndade - 4,22%, Abraão - 3,61%, Saco, Grande - 3,01%, Jardim Atlantico - 3,01% , Rio Tavares - 3,01%, Outros - 2%	ND	ND	ND	ND

dimensões	PILAR	TEMA	SUBTEMA		ORDEM CES	NOVA ORDE	ORDEM FLORIP	ÓRGÃO RESPONSÁVEL	INDICADOR	FAIXAS PARA SEMAFORIZAÇÃO			2019	2020	2021	2022	2023	2024
	REDUÇÃO DA VULNERABILIDADE DIANTE DE DESASTRES NATURAIS E ADAPTAÇÃO À MUDANÇA DO CLIMA	VULNERABILIDADE FRENTE A DESASTRES NATURAIS NO CONTEXTO DA MUDANÇA CLIMÁTICA	CAPACIDADE DE ADAPTAÇÃO À MUDANÇA CLIMÁTICA E A EVENTOS NATURAIS EXTREMOS	28	30	28		SMSP/ Defesa Civil	Mapas de risco: porcentagem das áreas sujeitas a riscos decorrentes de deslizamentos, inundações costeiras e fluviais, mapeadas na escala 1:10.000, com grau de risco alto, médio ou baixo risco.	acima de 90%	de 60 a 89,99%	abaixo de 60%	100%	100%	**100%**	**100%**	100%	90%
				29	34	29		SMSP	Porcentagem das áreas de risco e vulnerabilidades da cidade (áreas de risco de deslizamento, de inundação costeira e pluvial, de vulnerabilidade social, de interrupções das pontes, de secas com comprometimento de abastecimento de água, apagões e de congestionamento viário extremo) que possuem planos de contingência adequados e atualizados.	acima de 90%	de 60 a 89,99%	abaixo de 60%	100%	100%	**100%**	**100%**	100%	100%
				30	35	30		SMSP	Porcentagem dos planos de contingência de riscos que possui alerta precoce	acima de 90%	de 60 a 89,99%	abaixo de 60%	100%	100%	**100%**	**100%**	100%	100%
				31	38	31		SMSP	Porcentagem da Lei Orçamentária Anual (LOA) planejados para mitigação dos riscos de desastres naturais e mudanças climáticas	acima de 0,5%	0,5 a 0,3%	abaixo de 0,3%	0,42% (Lei 10.672-2019, total do orçamento R$ 2.357.582.046,00)	0,076% LOA 2021	**0,100% LOA 2022 (Lei 10.832/2021)**	**0,125% LOA 2022 Lei 10.832/2021**	0,120% LOA 2023 (Lei 10.945/2022	0,07 LOA (Lei 11.344/2024)
			SUSTENTABILIDADE A DESASTRES NATURAIS	32		32	6.5.2	SMSP/ Defesa Civil/FRN	Número de edificações em áreas de risco.							**1080 unidades**	1593 unidades	2100 unidades
			DENSIDADE	33	41	33		IPUF	Porcentagem de crescimento anual da quilometragem da malha urbana	< 3%	3%–5%	> 5%	0,56%	2,43%	**1,86%**	**0,84%**	ND	1,41%
				34	42	34		IPUF	Quantidade de população por km² de área urbanizada (exclui-se as áreas de agricultura e açudes de mais de 5 km)	7.000 - 20.000	4.000–7.000; 20.000–25.000	< 4.000; > 25.000	De 4.977,24 hab/km² para 5.017,22% hab/km²	De 5.055,26 hab/km² para 4.975,08 hab/km2²	**4.958,28 hab/km²**	**5.113,88 hab/km²**	ND	ND
				35	L 8	35		IPUF	Porcentagem de crescimento demográfico	<1%	1% - 1,5%	> 1,5%	1,62%	1,57%	**1,51%**	**4,01%**	ND	ND
				36		36	5.1.4	IPUF/FNR	Porcentagem de pessoas vivendo em moradias inadequadas em relação à população total.				2.52%				ND	ND

dimensões	PILAR	TEMA	SUBTEMA		ORDEM CES	NOVA ORDE	ORDEM FLORIP	ÓRGÃO RESPONSÁVEL	INDICADOR	FAIXAS PARA SEMAFORIZAÇÃO			2019	2020	2021	2022	2023	2024
		USO DO SOLO / ORDENAMENTO TERRITORIAL	ÁREAS VERDE E DE RECREAÇÃO	37	44	37		SMDU	Déficit de moradias quantitativo	< 10%	10%–20 %	> 20%	Déficit habitacional quantitativo é de 7.872 unidade a necessidade de reassentamentos é de 1.666 habitações	ND	**Estimativa do déficit habitacional quantitativo em ZEIS: 7.842**	Déficit quantitativo 21.705 famílias = 52% (Total 41.804 famílias do CadÚnico estão enquadradas nos critérios definidos)	Déficit quantitativo 21.705 famílias =52% (Total 41.804 famílias do CadÚnico estão enquadradas nos critérios	ND
				38	45	38		IPUF	Quantidade de hectares de áreas verdes permanentes de lazer (de acordo com o Plano Diretor) para cada 100.000 habitantes (população projetada IBGE)	> 50	20–50	< 20	De 5786,66 hectares/100,000hab para 6.088,92 hectares/100,000hab	De 5.710,10 hectares / 100.000 habitantes para 6.088,77 hectares / 100.000 habitantes	**5.565,61 hectares/100.000 habitantes**	5.438,05 hectares/100.000 habitantes	ND	ND
				39		39	1.5.3	IPUF/FNR	Espaços livres de lazer e recreação de uso público excluídas áreas de estacionamento (m² per capita)					2.62 m²/hab	ND	ND	ND	ND
				40	**NOVO**	40		IPUF	Porcentagem das edificações em áreas de conflito ambiental: quantidade de edificações irregulares dividido pelo total das edificações.	< 0,5%	0,6% - 2%	> 2 %	9,28%	10,65%	**9,24%**	9,69%	ND	ND
				41	L 10	41	6.1.1	FLORAM	Áreas naturais protegidas: porcentagem de Unidades de Conservação (UC) com plano de manejo.	acima de 90%	de 60 a 89,99%	abaixo de 60%	De 27,95% (considerando todas as UC) 0,30% (considerando somente UC com plano de manejo) para 27,15% (total UC) 2,79% (com plano de manejo)	27,15% (total UC) 6,42% (com plano Manejo)	**41,26% (total das UC) 8,14% (UC com plano de manejo)**	**41,6**	ND	20%(Considerando 10 Ucs de gestão Municipal)

dimensões	PILAR	TEMA	SUBTEMA		ORDEM CES	NOVA ORDE	ORDEM FLORIP	ÓRGÃO RESPONSÁVEL	INDICADOR	FAIXAS PARA SEMAFORIZAÇÃO			2019	2020	2021	2022	2023	2024
	CONTROLE DO CRESCIMENTO E MELHORIA DO HABITAT URBANO			42		42	6.1.2	IPUF/FNR	Porcentagem da área total terrestre do município designada para proteção ambiental por meio de legislação federal, estadual ou municipal.							**59,60%**	59,6%(2022)	59,6%(2022)
			PLANEJAMENTO DO SOLO	43	L 4	43	1.9.1	SMPIU	Porcentagem de área parcelada irregularmente sobre área urbanizável. (Floripa em Números = Núcelos Urbanos informais)	< 10%	10% - 25%	> 25%	36% de mancha urbana com indicativo de irregularidades urbanísticas e fundiárias no Município.	ND	**Total 36% Por Distrito: Barra da Lagoa: 50,58% Cachoeira do Bom Jesus: 48,07% Campeche: 71,80% Canasvieiras: 16,58% Ingleses do Rio Vermelho: 66,35% Lagoa da Conceição: 38,39% Pântano do Sul: 42,98% Ratones: 34,09% Ribeirão da Ilha: 35,98% Santo Antônio de Lisboa: 16,26% São João do Rio Vermelho: 81,84% Sede: 17,49%**	**39,81%**	**37,89 %(base 2019, consulta 02/10/24)**	**ND**
				44		44	5.2.5	SEMAS/FNR	População vivendo abaixo da linha internacional de pobreza (porcentagem)								8,5% (PNAD 2022)	4,8% (PNAD 2023)

dimensões	PILAR	TEMA	SUBTEMA		ORDEM CES	NOVA ORDE	ORDEM FLORIP	ÓRGÃO RESPONSÁVEL	INDICADOR	FAIXAS PARA SEMAFORIZAÇÃO			2019	2020	2021	2022	2023	2024
		DESIGUALDADE URBANA	POBREZA	45		45	5.2.8	SEMAS/FNR	População vivendo abaixo da linha nacional de pobreza (porcentagem)							**9,11%**	4,81% (https://www.negociossc.com.br/noticia/compare-a-desigualdade-no-brasil-e-santa-catarina-em-3-dados/#:~:text=Percentual%20de%20pessoas%20em%20situa%C3%A7%C3%A3o%20de%20pobreza,14%2C98%25%20*%20Entorno%20Metropolitano%20de%20Florian%C3%B3polis:%2016%2C12%25)	4,81% (https://www.negociossc.com.br/noticia/compare-a-desigualdade-no-brasil-e-santa-catarina-em-3-dados/#:~:text=Percentual%20de%20pessoas%20em%20situa%C3%A7%C3%A3o%20de%20pobreza,14%2C98%25%20*%20Entorno%20Metropolitano%20de%20Florian%C3%B3polis:%2016%2C12%25)
			SEGREGAÇÃO SOCIOESPACIAL	48		46	1.9.3	SMDU/FNR	Percentual de moradias sem títulos legais de propriedade em relação ao número total de moradias.							**3,94 % / 100 mil hab**	3,94 % / 100 mil hab	ND
				49		47	5.1.4	SMDU/FNR	Percentual de pessoas vivendo em moradias inadequadas em relação à população total.				2.52%				2,52 % / 100 mil hab (2019)	ND
				50		48	5.1.6	SMDU/FNR	Pessoas em situação de rua (por 100 mil habitantes)								1.002 / 100 mil hab	ND
			DESIGUALDADE DE RENDA	51	51	49	5.2.10	SEMAS/FRN	Coeficiente de Gini da renda (Fonte: PENAD Contínua do IBGE)	< 0,40	0,40–0,49	> 0,49	0,54 (2010)	0,54	0,54 (2010)	0,419 (FIESC 2022)	0,419 (FIESC 2022)	0,4 (IBGE 2023)
				52	L 17	50		SMTTDE	Remuneração média dos trabalhadores formais (Fonte: Secretaria do Trabalho - RAIS)	Acima de R$ 3.280	R$ 2.569 a R$ 3.280	R$ 788 a R$ 2.568	ND	ND Ainda não foram publicados os dados de 2020	**R$ 5.411,68 (Ano base de 2020. Ainda não foram publicados os dados de 2021)**	R$ 5.459,98 Fonte: RAIS ano base 2021 - ainda não foram publicado os dados de 2022	ND	ND
				53	52	51		SMPIU	Quilômetros de vias públicas por 100 mil habitantes (População projetada do IBGE)	< 300	300–400	> 400	357,49	352,68 km/100 mil hab.	**347,73 km**	**334,3 km/**	**334,3 km/(base 2022)**	ND
				54	**NOVO**	52	2.5.3	SMPU	Porcentagem de vias públicas não pavimentadas em relação ao total de quilômetros de vias públicas	< 5%	5%-10%	> 10%	40,39%	ND	**ND**	6.65% (2022)	6.65% (2022)	ND

dimensões	PILAR	TEMA	SUBTEMA		ORDEM CES	NOVA ORDE	ORDEM FLORIP	ÓRGÃO RESPONSÁVEL	INDICADOR	FAIXAS PARA SEMAFORIZAÇÃO			2019	2020	2021	2022	2023	2024
	PROMOÇÃO DO TRANSPORTE URBANO SUSTENTÁVEL	MOBILIDADE / TRANSPORTE	INFRAESTRUTURA DE TRANSPORTE EQUILIBRADA	55		53	2.1.5	SMTI/FNR	Comprimento total (km) dos sistemas de transporte público em operação na cidade dividido pela população total da cidade, expresso km por 100.000 habitantes.							**1.282,34 por 100 mil hab**	1.282,34 km/100 mil hab (2022)	1.282,34 km/100 mil hab (2022)
				56	53	54	2.1.4	SMTI	Quilômetros de vias dedicadas exclusivamente ao transporte público por 100 mil habitantes (população projetada do IBGE)	> 40	10–40	< 10	0%	0%	**ND**	**0,197**	ND	0,31
				57	54	55	somar: 2.2.2 + 2.2.3 + 2.2.4	SMTI/FNR	Quilômetros de ciclovias, ciclofaixas e ciclorotas por 100 mil habitantes (população projetada IBGE)	> 25	15–25	< 15	25,01	Km total de infraestrutura cicloviária: 164,81 km / 508.826 = **32,39 km / 100 mil habitantes.**	**35,89 KM**	**40,06 km/ 100 mil habitantes.**	**25,89 km / 100 mil hab**	**26,81 km / 100 mil hab**
				58	**NOVO**	56		SMTI	Porcentagem de km de ciclovias, ciclofaixas e ciclorotas em relação ao total de km de vias da cidade	>25%	25%-15%	<15%	1,51%	164,81 km / 1.794,54 km = **9,18%**	**10,32%**	**11,98%**	11.98%	154,52 km / 1.794,54 km = 8,61%
				59	55	57		SMTI	Quilômetros de calçadas e calçadões pavimentados, por 100 mil habitantes (população projetada pelo IBGE)	Mais de quatro vezes a extensão da rede de rodovias	Entre duas e quatro vezes a extensão da rede de rodovias	Menos de duas vezes a extensão da rede de rodovias	ND	ND	**ND**	**ND**	ND	ND
				60	**NOVO**	58		SMTI	Porcentagem de km de calçadas e calçadões pavimentados, em relação ao total de km de vias	>70%	70%-50%	<50%	ND	ND	**ND**	**60%**	60%	60%
				61	**NOVO**	59		SMTI	Quilometragem média/mês rodada pela frota de transporte público	sem valor de referência			2.862.446 km	1.273.214,96 km/mês média	**1 853 096,91**	**2.750.000**	2.811.300	2.734.075
				62	**NOVO**	60		SMTI	Quantidade média/mês de pessoas transportadas pelo transporte público	sem valor de referência			175.378	1.768.150,67 passageiros/ mês.	**2 569 218,33**	**4.603.849**	4.902.930	4.934.532
				63	**NOVO**	61		SMTI	Custo anual do sistema de transporte público (subsídio + custo do consórcio) por pessoa transportada	sem valor de referência			R$ 4.25	ND	**ND**	**R$ 5,27**	R$ 5,32	R$ 5,84
				64	**NOVO**	62		SMTI	Velocidade média/mês da frota de transporte público	>30%	30%–15 %	< 15%	23 km/h	ND	**24,23 km/h**	**23,53 KM/H**	23,00 km/h	22.91

dimensões	PILAR	TEMA	SUBTEMA		ORDEM CES	NOVA ORDE	ORDEM FLORIP	ÓRGÃO RESPONSÁVEL	INDICADOR	FAIXAS PARA SEMAFORIZAÇÃO			2019	2020	2021	2022	2023	2024
				65	**NOVO**	63		SMTI	Média/mês da capacidade ofertada para o transporte de pessoas no sistema de transporte público	sem valor de referência			ND	7.351.979 média/mês da capacidade ofertada.	**12.800.000**	**16.300.000**	**14.442.624**	**16.099.959**
				66	56	64		SMTI	Distribuição modal: porcentagem do transporte realizado via bicicleta, barco, taxi, aplicativo, carro particular e ônibus.	> 65%	50%–65 %	< 50%	ND	ND	**ND**	**ND**	ND	ND
				67	**NOVO**	65		SMTI	Média/litros/mês do consumo de óleo diesel da frota de transporte público (Fonte: Consórcio Fênix)	sem valor de referência			0,3438 l/km	ND	**ND**	**834.462**	1.062.886	1.222.319
			TRANSPORTE LIMPO	68	**NOVO**	66		SMTI	Porcentagem da frota de transporte público movida a energia elétrica	> 20%	20%–10 %	< 10%	0%	0%	**0%**	**0%**	0%	0%
			TRANSPORTE LIMPO	69	**NOVO**	67		SMTI	Porcentagem da frota de transporte público com ar condicionado	> 70%	70%–50 %	< 50%	18,50%	19,74%	**19,75%**	**18,00%**	18,00%	4,00%
			TRANSPORTE LIMPO	70	57	68		SMTI	Idade média da frota do transporte público	< 6	6–12	> 12	5,9 anos	6,78 anos.	**7 anos e 9 meses**	**8 anos e 6 meses**	8,43 anos	8,94
			TRANSPORTE SEGURO	71	58	69	10.2.1	SSP/FNR	Vítimas mortais de acidentes de trânsito por 100 mil habitantes	< 10	10–20	> 20	10.18	7,30	5,600	**5,9**	6,100	8,5
			TRANSPORTE SEGURO	72	**NOVO**	70		SMS	Quantidade anual de pessoas hospitalizadas por acidentes de trânsito por 100.000 habitantes (população projetada IBGE)	sem valor de referência			23.15	14.80	**18.18**	20.36	12.91	10.58
			MENOS CONGESTIONAMENTO	73	59	71		SMTI	Velocidade média de viagem (transporte público e privado) nas principais vias públicas durante os horários de pico	> 30	15–30	< 15	17 km/h	ND	**ND**	**20,12**	19,75	21.81
			MENOS CONGESTIONAMENTO	74	60	72	**2.4.1**	SMTI/FNR	Número de veículos de uso pessoal (automóveis, SUV's, etc) registrados no DETRAN local (exceto táxis) per capita (população projetada IBGE)	< 0,3	0,3–0,4	> 0,4	0,63	0,63	**0,638**	**0,722**	**0,65**	0,723
			TRANSPORTE ECONÔMICO	75	62	73		SMTI	Índice de acessibilidade (Salário Mínimo Nacional/(44 viagens mês* valor da tarifa em dinheiro))	Até 5%	5%–10%	> 10%	5,15	5,27	**6,12**	**5,00**	R$1.412,00/(44*R$6,00) = 5,35	4,65
		AMBIENTE DE NEGÓCIOS	REG. NEGÓCIOS E INVESTIMENTOS	76	65	74		SMDECT	Quantidade de dias para abrir uma empresa	< 12	12–20	> 20	Baixo Risco - Mesmo Dia (4 horas) Outras Categorias de Risco - em até 15 dias	1 dia e 19 horas	**1 dia e 1 hora (Mapa de Empresas, Ministério da Economia)**	12 horas	12 horas	5 horas

dimensões	PILAR	TEMA	SUBTEMA		ORDEM CES	NOVA ORDE	ORDEM FLORIP	ÓRGÃO RESPONSÁVEL	INDICADOR	FAIXAS PARA SEMAFORIZAÇÃO			2019	2020	2021	2022	2023	2024
			GESTÃO ESTRATÉGICA DA INFRAESTRUTURA	77	**NOVO**	75		FLORIPA AIRPORT	Tonelada de carga transportada pelo aeroporto em comparação com a sua capacidade máxima (Fonte: Infraero e aeroporto)	sem valor de referência			ND	ND	**ND**	2.500 toneladas Carga Internacional 3.550 toneladas carga doméstica	3.070 toneladas Carga Internacional 5.284 toneladas carga doméstica	6.568 toneladas Carga Internacional 6.578 toneladas carga doméstica
				78	**NOVO**	76		FLORIPA AIPORT	Quantidade de pessoas transportadas pelo aeroporto ano- Consultar Infraero e aeroporto	sem valor de referência			ND	ND	**ND**	3.393.219 de passageiros em 2022	3.955.113 de passageiros em 2023	4.895.252 de passageiros em 2024
				79	**NOVO**	77		SIE e Adm da Rodoviária Rita Maria (SINART ORGANIZAÇÕES)	Quantidade de viagens de ônibus ano (chegadas e saídas no ano) (indicador novo 2024)	sem valor de referência								Chegados= 72.618 Saidos/Transito = 76.440 Total= 149.058
				80	**NOVO**	78		SIE	Quantidade de pessoas transportadas pela rodoviária ano (Fonte: rodoviária e Deter)	sem valor de referência			ND	ND	**ND**	Chegados=791.428 + Saidos = 850.637 Total 1.642.065	Chegados= 985.834 Saidos=1.037.721 Total= 2.023.555	Chegados= 1.218.210 Saidos=1.282.326 Total= 2.500.536
				81	67	79	8.2.1	SMDECT/SIE/FRN	PIB per capita da cidade (Fonte IBGE - Estatisticas)	>US$ 9.000	US$ 3.000–US$ 9.000	< US$ 3.000	43.847 (U$ 4.0795)	41.886 (U$ 5,4854)	**45.603 (U$ 5.5748)**	R$ 41.885,53 Fonte: IBGE ano base 2020	PIB Per Capita 2021 R$ 45.602,98/PIB Per Capita 2020 R$ 41.885,53)	45.602,98 R$ [2021]

dimensões	PILAR	TEMA	SUBTEMA		ORDEM CES	NOVA ORDE	ORDEM FLORIP	ÓRGÃO RESPONSÁVEL	INDICADOR	FAIXAS PARA SEMAFORIZAÇÃO			2019	2020	2021	2022	2023	2024
	PROMOÇÃO DO DESENVOLVIMENTO ECONÔMICO LOCAL COMPETITIVO SUSTENTÁVEL	TECIDO PRODUTIVO	CRESCIMENTO PRODUTIVO	82	68	80		SMTDI	Taxa de crescimento do PIB per capita da cidade (Fonte: IBGE Estatísticas)	> 2,5% O crescimento do PIB per capita da cidade é positivo e superior ao crescimento do PIB nacional (2)	2-2,5% O crescimento do PIB per capita da cidade é positivo e igual ou similar ao crescimento do PIB nacional (1)	<2% O crescimento do PIB per capita da cidade é positivo e igual ou similar ao ao crescimento do PIB nacional (0)	2,85%	6,36%	**2,63% (Cálculo com base no indicador do ano anterior!)**	- 4,46% Fonte: IBGE - ano base 2020 (renda percapita ano atual/renda per capita ano anterior)	1,08%	1,08%
				83	L 13	81		Secretaria Executiva de Desenvolvimento Econômico, Ciência e Tecnologia	Porcentagem do PIB de Florianópolis em relação ao PIB de SC	> maior que a inflação	igual a inflação	< que a inflação	ND	14,% (inflação 4,51%)	**6,79 % (inflação 10,06%)**	**6,1% (inflação 5,78%)**	**5,48% (2021) (Inflação 10,06%)**	**5,5% (2021) (Inflação 4,83%)**

dimensões	PILAR	TEMA	SUBTEMA		ORDEM CES	NOVA ORDE	ORDEM FLORIP	ÓRGÃO RESPONSÁVEL	INDICADOR	FAIXAS PARA SEMAFORIZAÇÃO			2019	2020	2021	2022	2023	2024
				84	EBA 1	82		SMTDI	Taxa de crescimento do PIB da cidade (Fonte: IBGE Estatisticas)	>3,5% O crescimento do PIB da cidade é positivo e superior ao crescimento do PIB nacional (2)	3-3,5% O crescimento do PIB da cidade é positivo e igual ou similar ao crescimento do PIB nacional (1)	<3% O crescimento do PIB da cidade é positivo e igual ou similar ao ao crescimento do PIB nacional (0)	ND	7,90%	**2,60%**	2,97% Fonte: IBGE - ano base 2020 (PIB ano atual/PIB ano anterior)	10% (IBGE)	ND
		MERCADO LABORAL	DESEMPREGO	85	69	83	8.1.5	SMTDI /FNR	Taxa de desemprego (Fonte: IBGE - ESTATISTICAS - PNAD Contínua)	< 7%	7%–12%	> 12%	8,30% (jan, fev, mar 2020)	ND	**ND**	5,37%	4,30%	4,40%
			EMPREGO FORMAL	86	**NOVO**	84	8.1.7	SMTDI /FNR	Porcentagem da população ocupada - Formal (Fonte: IBGE - ESTATISTICAS - PNAD Contínua) https://cidades.ibge.gov.br/brasil/sc/florianopolis/panorama	> 75%	75% - 65%	< 65%	63,90%	ND	**ND (PNAD Contínua somente traz dados de SC)**	72% Fonte: PNAD continua, painel, ano base 2019 - taxa de ocupação e não formalidade	63,72% (2010)	64,40%
			EMPREGO INFORMAL	87	70	85		SMTDI	Emprego informal como porcentagem do emprego total (Fonte: IBGE - ESTATISTICAS - PNAD Contínua) https://cidades.ibge.gov.br/brasil/sc/florianopolis/panorama	< 20%	20%–35 %	> 35%	ND	ND	**ND (PNAD Contínua somente traz dados de SC)**	28,4% Fonte: PNAD continua, painel, ano base 2019 (taxa de informalidade = 100 - taxa de formalidade)	27,50%	ND
URBANO			O	89	76	86		SME	Taxa de analfabetismo de pessoas acima de 15 anos	< 0,5%	0,5% - 2%	> 2%	1,60%	1,60% (dados de 2019)	**ND**	1,60% (dados de 2019)	1,10%	1,4% (https://educa.ibge.gov.br/jovens/conheca-o-brasil/territorio/22321-alfabetizacao.html)

dimensões	PILAR	TEMA	SUBTEMA		ORDEM CES	NOVA ORDE	ORDEM FLORIP	ÓRGÃO RESPONSÁVEL	INDICADOR	FAIXAS PARA SEMAFORIZAÇÃO			2019	2020	2021	2022	2023	2024
		EDUCAÇÃO	QUALIDADE DO ENSINO	90	77	87		SME	Porcentagem de Estudantes do ensino fundamental com nível satisfatório em provas padronizadas (IDEB) de Leitura	>=70%	69%–50 %	> 50%	35%(2019)	35%(2019)	35%(2019)	35%(2019)	43% (2021)	31% (https://qedu.org.br/municipio/4205407-florianopolis -filtro: municipal)
						88		SME	Nota IDEB dos anos iniciais	>6	6-5	<5	6	6(2019)	5,9	5,9(2021)	5,8	5.8(2023)
						89		SME	Nota IDEB dos anos finais	>6	6-5	<5	4,9	4,9(2019)	5,2	5,2(2021)	4,6	4,6(2023)
				91	78	90		SME	Porcentagem de Estudantes do ensino fundamental com nível satisfatório em provas padronizadas (IDEB) de Matemática	>=70%	69%–50 %	> 50%	19% (2019)	19% (2019)	19%(2019)	18% (2021)	18% (2021)	14,% ((https://qedu.org.br/municipio/4205407-florianopolis -filtro: municipal)
						91		SME	Quantidade de professores (Efetivos) na Educação Básica do Município	>60%	60%-50%	<50%	1004 (50%)	975 (47,5%)	996 (49,5%)	1193 (51,1%)	1131 (44,4%)	954 (39,30%)
						92		SME	Quantidade de professores (ACTs) na Educação Básica do Município	<50%	50%-60%	>60%	1001 (49,9%)	1078 (52,5%)	1015 (50,5%)	1140 (48,9%)	1417 (55,6%)	1471 (60,7%)
						93		SME	Porcetagem de profisisonais da educação com especialização (efetivos + substitutos)	>60%	60%-40%	<40%						61,07%
						94		SME	Porcetagem de profisisonais da educação com mestrado (efetivos + substitutos)	>20%	20%-10%	<10%						13,12%
						95		SME	Porcetagem de profisisonais da educação com doutorado (efetivos + substitutos)	>5%	5%-4%	<4%						4,17%
						96		SME	Percentual de alunos da educação básica pública que pertencem ao público alvo da ETI e que estão em jornada de tempo integral(Rede Municipal) - Meta 6A	>=25%	20 - 24,9%	<19,9	32,1%%	24,70%	24,00%	27,30%	27,10%	
						97		SME	Percentual da população de 0 a 3 anos que frequenta a escola/creche.(Território) - Meta 1B Fonte TCE SC	>50%	<50-40	<40	53,15%	44,69%	40,06%	45,91%	59,60%	
						98		SME	Percentual da população de 4 a 5 anos que frequenta a escola/creche .(Território) - Meta 1A - Fonte TCE SC	95-100 %	<95-90	<90	89,59%	86,21%	76,79%	81,42%	97,89%	
				94	81	99		SME	Percentual da população de 6 a 14 anos que frequenta ou que já concluiu o ensino fundamental Meta 2 A - Fonte TCE SC	95-100	<94	<90	103,40% IBGE	96,51% TCE SC	96,03% TCE SC	99,18% TCE SC	106,18% TCE SC	
				95	82	100		SME	Número de estudantes matriculados nos anos finais do ensino fundamental - que esta cursando o ensino médio ou concluiu o ensino fundamental (15 a 17 anos) Meta 3 B - IBGE	95-100	<94	<90	71,80%	72,70%	73,40%	83,31%	74,60%	

dimensões	PILAR	TEMA	SUBTEMA		ORDEM CES	NOVA ORDE	ORDEM FLORIP	ÓRGÃO RESPONSÁVEL	INDICADOR	FAIXAS PARA SEMAFORIZAÇÃO			2019	2020	2021	2022	2023	2024
				97		101	4.1.3	SEE/FNR	Porcentagem de estudantes que completam o último ano do ensino médio em relação ao total de estudantes originalmente matriculados no primeiro ano do ensino médio.							54,7	ND	ND
				98	**NOVO**	102		SME	Número de estudantes público alvo da educação especial matriculadas na Educação Básica (0 a 17 anos)	sem valor de referência			841	905	952	1335	1716	1952
				99	**NOVO**	103		SME	Porcentagem das escolas que cumprem a Lei de Acessibilidade	> 95%	95% - 90%	< 90%	Não é levantado pelo município.	91% ou seja, 106 unidades educativas da rede municipal possuem dependências acessíveis	**95,07%**	96,46 %	96,19%	96,21%
			ENSINO SUPERIOR	100		104	4.1.6	SME/FNR	Número de pessoas com ensino superior completo acima de 25 anos (por 100 mil habitantes)					271711 (+ 25 anos TOTAL)	**271711**	**383891**	**383891**	**383891**
			VIOLÊNCIA	101	85	105	10.1.5	SSP/FNR	Quantidade de homicídios por 100 mil habitantes - população projetada pelo IBGE	< 10	10–25	> 25	12,2	10,60	**6,90**	**6,40**	4,50	5,40
				102	**NOVO**	106		SSP	Quantidade de latrocínios por 100.000 habitantes - população projetada pelo IBGE	<5	5-10	>10	0,0	0,20	**0,00**	**0,30**	0,20	0,00
				103	**NOVO**	107		SSP	Quantidade de feminicídios por 100.000 habitantes mulheres - população projetada pelo IBGE	<5	5-10	>10	Nº de vítimas: 1	0,70	**0,70**	**0,50**	0,20	0,50
				104	86	108		SSP	Número de ocorrências de violência doméstica em mulheres				Nº de ocorrências de lesão corporal dolosa em situação de violência doméstica. Vítimas do sexo masculino: 154; Vítimas do sexo feminino: 1.081 = 247 por 100 mil hab	**5.342**	**5.815**	**6.077**	**6.865**	**5864** (Estimativa de população feminina: 300.000 Nr/100 mil =34.502)

dimensões	PILAR	TEMA	SUBTEMA		ORDEM CES	NOVA ORDE	ORDEM FLORIP	ÓRGÃO RESPONSÁVEL	INDICADOR	FAIXAS PARA SEMAFORIZAÇÃO			2019	2020	2021	2022	2023	2024
	OS SOCIAIS DE ALTO NÍVEL E PROMOÇÃO DA COESÃO SOCIAL	SEGURANÇA		105	88	109		SSP	Roubos por 100 mil habitantes - população projetada pelo IBGE	< 300	300–1.000	> 1.000	324,2	205,8	**194,3**	**139,8**	144,5	153
				106	89	110		SSP	Furtos por 100 mil habitantes - população projetada pelo IBGE	< 3.000	3.000–5.000	> 5.000	2326,3	1616,20	**1600,40**	**2242,50**	2770,1	2661,4
				107	**NOVO**	111		SSP	Furtos de veículos por 100 mil habitantes - população projetada pelo IBGE	<100	100-150	>150	92,0	67,70	**64,70**	**64,00**	71	66,5
				108	**NOVO**	112		SSP	Roubos de veículos por 100 mil habitantes - população projetada pelo IBGE	<50	50-75	>75	40,5	21,50	**20,10**	**16,00**	16,8	13,9
				109		113	10.1.10	SSP/FNR	Crimes contra a propriedade por 100 000 habitantes	<50	50-75	>75		18,4	**21**	**9,5**	10,9	8,8
			ESTRUTURAS DE SEGURANÇA	110	L 20	114		SSP	Quantidade de CONSEGs ativos	sem valor de referência			Esta Gerência não tem essa informação	8 CONSEGS ativos	**ND**	8 ATIVOS: 1 CONSEG Centro 2 CONSEG Portal do Sul da Ilha 3 CONSEG Barra da Lagoa 4 CONSEG Canasvieiras 5 CONSEG Ingleses e Rio Vermelho 6 CONSEG Jurerê, Forte e Daniela 7 CONSEG Coqueiros 8 CONSEG Balneário do Estreito (Fonte Rodrigo Marques Presidente CONSEG Centro)	ND	ND
				111	**NOVO**	115		SMS	Taxa Geral de mortalidade por 100.000 habitantes (População projetada IBGE)	sem valor de referência			476.98	543.56	**647.08**	568.26	545.65	518.60
				112	**NOVO**	116		SMS	Taxa Geral de mortalidade de homens por 100.000 habitantes (População projetada IBGE)	sem valor de referência			520.16	601.56	**712.32**	633.41	569.40	548.67
				113	**NOVO**	117		SMS	Taxa Geral de mortalidade de mulheres por 100.000 habitantes (População projetada IBGE)	sem valor de referência			436.52	489.72	**586.58**	507.57	523.64	490.40

dimensões	PILAR	TEMA	SUBTEMA		ORDEM CES	NOVA ORDE	ORDEM FLORIP	ÓRGÃO RESPONSÁVEL	INDICADOR	FAIXAS PARA SEMAFORIZAÇÃO			2019	2020	2021	2022	2023	2024
	OFERTA DE SERVIÇC		NÍVEL DE SAÚDE	114	95	118	3.1.4	SMS/FNR	Taxa de mortalidade infantil (crianças menores de 5 anos)por 100.000 habitantes (População projetada IBGE)	< 20	20 -30	> 30	5.22	7.78	**6.10**	7.73	6,37	6.90
				115	**NOVO**	119		SMS	Taxa de mortalidade Precoce (Anos potenciais de vida perdido - APVP) por 100.000 habitantes (População projetada IBGE)	sem valor de referência			4113.40	4488.74	4940.25	4432.35	4238.98	3884.54
				116	**NOVO**	120		SMS	Taxa de mortalidade por doenças cardovasculares por 100.000 habitantes (População projetada IBGE)	sem valor de referência			137.95	138.42	141.98	152.47	154.18	141.40
				117	**NOVO**	121		SMS	Taxa de mortalidade por neoplasias por 100.000 habitantes (População projetada IBGE)	sem valor de referência			130.10	134.48	142.53	154,9	149.23	140.19
				118	**NOVO**	122		SMS	Taxa de mortalidade por causas externas (acidentes, crimes, etc.) por 100.000 habitantes (População projetada IBGE)	sem valor de referência			35.59	39.89	46.65	50.82	46.86	44.59
				119	**NOVO**	123		SMS	Taxa de internação de adultos por 100.000 habitantes (População projetada IBGE)	sem valor de referência			5305.46	4260.80	4423.44	4746.20	5254.74	4940.43
				120	**NOVO**	124		SMS	Taxa de internação de crianças por 100.000 habitantes (População projetada IBGE)	sem valor de referência			3987.56	2688.84	3150.18	4352.32	4932.08	4684.31
				121	**NOVO**	125		SMS	Taxa de internação por causas externas (acidentes, crimes, etc.) por 100.000 habitantes (População projetada IBGE)	sem valor de referência			589.87	452.53	506.75	534.38	644.14	566.14
				122	**NOVO**	126		SMS	Taxa de internação por doenças cardiovasculares por 100.000 habitantes (População projetada IBGE)	sem valor de referência			473.35	375.54	**395.26**	418.49	455.83	428.72
				123	**NOVO**	127		SMS	Taxa de internação por neoplasias por 100.000 habitantes (População projetada IBGE)	sem valor de referência			430.87	385.85	**416.39**	466.61	461.31	527.97
				124	L 22	128		SMS	Prevalência de Diabetes Millitus: Percentual da população atendida nos hospitais e postos de Saúde pública que tem diabetes - População projetada pelo IBGE	sem valor de referência			6.12	7.95%	**6.44%**	ND	7.27	ND
				125	L 23	129	3.1.9	SMS/FNR	Prevalência de obesidade: Percentual de indivíduos, com Índice de Massa Corporal (IMC) maior ou igual a 25 (População projetada pelo IBGE)	sem valor de referência			17.62	17.51%	**20.17%**	20,20%	21.91	ND
				126	L 24	130		SMS	Prevalência de Hipertensão: Percentual de pessoas com diagnóstico de hipertensão (População projetada pelo IBGE)	Abaixo de 5,7%	5,7% a 7,14%	Acima de 10%	21.61	22.09%	**24.31%**	23,30%	22.08	ND
				127	96	131	3.1.3	SMS/FNR	Quantidade de médicos por 100 mil habitantes (População projetada pelo IBGE)	> 200	75 - 200	< 75	2004.87	2155.81	**240143**	**2759.53**	2963.17	3060.03

dimensões	PILAR	TEMA	SUBTEMA		ORDEM CES	NOVA ORDE	ORDEM FLORIP	ÓRGÃO RESPONSÁVEL	INDICADOR	FAIXAS PARA SEMAFORIZAÇÃO			2019	2020	2021	2022	2023	2024
		SAÚDE	OFERTA DE SERVIÇOS DE SAÚDE	128	97	132		SMS	Quantidade de leitos de hospital por 100 mil habitantes, em hospitais públicos e privados	> 100	50 - 100	< 50	313.41	321.54	**344.05**	**353.86**	356.21	347.02
				129	**NOVO**	133		SMS	Quantidade de leitos de UTI em hospitais públicos e privados	sem valor de referência			42.31	57.77	**66.11**	**58.44**	51.60	52.93
				130	**NOVO**	134		SMS	Total de gasto do município com saúde pública por 100.000 habitantes	Sem valor de referência			94 938 073,88	97 262 531,48	95 367 635,02	102 122 757,78	99 745 048,06	111 441 182,76
				131	**NOVO**	135		SMS	Total do valor recebidos do Estado e do Governo Federal, destinados à saúde no município por 100.000 habitantes	Sem valor de referência			30 329 891,09	45 532 133,69	30 604 981,90	32 188 512,39	26 871 584,69	37 522 240,45
				132	**NOVO**	136		SMS	Cobertura de saúde da família: Média/mês de residências atendidas na modalidade de saúde da família	Sem valor de referência			97.98	82.22	**108.88%**	**103.77%**	104.73	108.39
				133	**NOVO**	137		SMS	Média/mês de pessoas atendidas nas UPAS e nos Postos de Saúde.	Sem valor de referência			27.401	131.151	169.786	203.685	210.034	213.306
				134	**NOVO**	138		ACM	Quantas vidas asseguradas em plano de saúde privada?	Sem valor de referência			179.209 (SMS)	187.504 total (tirando filantropia e Autogestão: 153.661)	**Planos de saude : 170.152 População de: 500.973 habitantes**	209.105	Grande Florianópolis : **345.085 e 299.703** (sem filantropia e autogestão)	ND
						139		SMS	Cobertura Vacinal - BCG - ao nascer	>=meta 90%	41 até <meta	<40					21,71%	39,17%
						140			Cobertura Vacinal - HEPATITE B - ao nascer	>=meta 95%	41 até <meta	<40					20,16%	34,94%
						141			Cobertura Vacinal - FEBRE AMARELA - menores 1 ano	>=meta 95%	41 até <meta	<40					64,83%	66,39%
						142			Cobertura Vacinal - HEPATITE B - menores 1 ano	>=meta 95%	41 até <meta	<40					79,58%	84,11%
						143			Cobertura Vacinal - DTP - menores 1 ano	>=meta 95%	41 até <meta	<40					79,60%	84,51%
						144			Cobertura Vacinal - MENINGO C - menores 1 ano	>=meta 95%	41 até <meta	<40					67,23%	72,80%
						145			Cobertura Vacinal - PENTAVALENTE - menores 1 no	>=meta 95%	41 até <meta	<40					79,57%	84,11%
						146			Cobertura Vacinal - PNEUMO 10 - menores 1 ano	>=meta 95%	41 até <meta	<40					78,46%	86,78%
						147			Cobertura Vacinal - POLIOMELITE injetável - menores 1 ano	>=meta 95%	41 até <meta	<40					79,11%	83,47%
						148			Cobertura Vacinal - ROTAVIRUS - menores 1 ano	>=meta 90%	41 até <meta	<40					76,55%	83,54%
						149			Cobertura Vacinal - HEPATITE A - 1 ano de idade	>=meta 95%	41 até <meta	<40					74,74%	74,32%

dimensões	PILAR	TEMA	SUBTEMA		ORDEM CES	NOVA ORDE	ORDEM FLORIP	ÓRGÃO RESPONSÁVEL	INDICADOR	FAIXAS PARA SEMAFORIZAÇÃO			2019	2020	2021	2022	2023	2024
						150			Cobertura Vacinal - DTP 1º reforço - 1 ano de idade	>=meta 95%	41 até <meta	<40					68,22%	74,77%
						151			Cobertura Vacinal - TRIPLICE VIRAL 1ª dose - 1 ano de idade	>=meta 95%	41 até <meta	<40					75,93%	85,61%
						152			Cobertura Vacinal - TRIPLICE VIRAL 2ª dose - 1 ano de idade	>=meta 95%	41 até <meta	<40					59,30%	58,04%
						153			Cobertura Vacinal - PNEUMO 10 1º reforço - 1 ano de idade	>=meta 95%	41 até <meta	<40					68,62%	79,68%
						154			Cobertura Vacinal - VARICELA - 1 ano de idade	>=meta 95%	41 até <meta	<40					53,92%	56,70%
						155			Cobertura Vacinal - POLIO ORAL LIVALENTE - 1 ano de idade	>=meta 95%	41 até <meta	<40					68,66%	80,61%
						156			Cobertura Vacinal - MENINGO C - 1 ano de idade	>=meta 95%	41 até <meta	<40					63,31%	67,83%
						157			Cobertura Vacinal - DTPA ADULTO	>=meta 95%	41 até <meta	<40					69,46%	75,39%
				135	L 21			SMS	Cobertura de vacinas	sem valor de referência			ND	- < 1 ano - Pentavalente - 3ªs doses - 45,7% - < 1 ano - Pneumocócica Conjugada 10v (PnC10v) - 2ªs doses - 54,8% - < 1 ano - Vacina contra Poliomielite - 3ªs doses - 48,2% - 1 ano - Tríplice Viral - 1ªs doses - 51,4%	**- < 1 ano - Pentavalente - 3ª dose - 73,10%** **- < 1 ano - Penumo 10 - 2ª dose - 76,40%** **- < 1 ano - VIP - 3ª dose - 72,30%** **- 1 ano VTV 1ª dose - 82,50%**	Febre amarela 69% Varicela 74% Meningo C 75% Rotavírus 81% Poliomielite 82% Pentavalente 82% Hepatite A 86% VTV 91% Penumo 10 93% BCG 113% (*(Em crianças de até* 01 ano)	Febre amarela 69% Varicela 50% Meningo C 70% Rotavírus 77% Poliomielite 74% Pentavalente 77% Hepatite A 78% VTV 80% Penumo 78% BCG 159%	Substituido pelos indicadores 140 até 158

dimensões	PILAR	TEMA	SUBTEMA		ORDEM CES	NOVA ORDE	ORDEM FLORIP	ÓRGÃO RESPONSÁVEL	INDICADOR	FAIXAS PARA SEMAFORIZAÇÃO			2019	2020	2021	2022	2023	2024
	COMPETITIVIDADE	CAPITAL HUMANO	CULTURA	136	L 18	158		SMF	Investimento em cultura per capita: por habitante (população projetada IBGE)	> R$ 26,83	R$ 17,88 a R$ 26,82	< R$ 17,87	R$ 29,59	R$ 2,32	**4,01 %**	**R$26,24**	R$ 58,22	R$ 52,26 (recursos próprios)
				137	L 19	159		SMF	Investimento em cultura sobre receita corrente líquida: total da receita líquida investida em cultura, no ano.	> R$ 2,47	R$ 1,77 a R$ 2,47	< R$ 1,76	R$ 0,69	0,58%	**0,60%**	**0,54%**	**1,04%** revisar parâmetros de semaforização para percentual	0,89%
			INTERNACIONALIZAÇÃO	138	99	160		SMTDI	Percentual de exportações de bens e serviços em relação ao PIB projetado IBGE do município (Fonte: http://comexstat.mdic.gov.br/pt/municipio - Exportações no SISCOMEX - Ministério da Economia e PIB do IBGE)	sem valor de referência			2019 - Valor FOB (US$) Florianópolis - SC $33.980.716	2020 - Valor FOB (US$) Florianópolis - SC $26.406.990	**2021 - Valor FOB (US$) Florianópolis - SC $40.839.598**	(US$)46.283.170	US$ 51.811.796	US$ 65.232.646
				139	102	161		SMTDI	Incremento anual da quantidade de empresas - Porcentagem de novas empresas abertas no ano (inclui todos os tamanhos de empresas)	sem valor de referência			Aprox. 20%	27%	**24% 2020 = 97811 empresas - novas em 2021 = 23786 - fonte: Mapa de Empresas/ME**	22% Fonte: mapa de empresas, ano base 2022 (novas empresas/ empresas ativas)	21%	21%
				140	**NOVO**	162		SMF	Porcentagem de variação do faturamento, em relação ao ano anterior, das empresas de tecnologia	sem valor de referência			18,46	113,87%	**ND**	**34,22%**	25,07%	28,39%
				141	**NOVO**	163		SMF	Porcentagem de participação da receita de impostos cobrados do setor de tecnologia em relação aos impostos totais	sem valor de referência			15,64	1,83%	**ND**	**26,70%**	15,78%	18,87%
				142	**NOVO**	164		SMF	Porcentagem de variação do faturamento, em relação ao ano anterior, das empresas de hotelaria e pousadas	sem valor de referência			-17,99	59,18%	**ND**	**70,71%**	29,62%	35,21%
				143	**NOVO**	165		SMF	Porcentagem de participação da receita de impostos cobrados do setor de saúde privada em relação aos impostos totais	sem valor de referência			1,9	1,03%	**ND**	**15,90%**	5,86%	6,32%

dimensões	PILAR	TEMA	SUBTEMA		ORDEM CES	NOVA ORDE	ORDEM FLORIP	ÓRGÃO RESPONSÁVEL	INDICADOR	FAIXAS PARA SEMAFORIZAÇÃO	2019	2020	2021	2022	2023	2024
		TECIDO EMPRESARIAL	DESENVOLVIMENTO EMPRESARIAL	144	NOVO	166		SMF	Porcentagem de variação do faturamento, em relação ao ano anterior, das empresas de saúde privada	sem valor de referência	739,01	109,31%	**ND**	**21,16%**	18,61%	15,52%
				145	NOVO	167		SMF	Porcentagem de participação da receita de impostos cobrados do segmento de hotelaria e pousada em relação aos impostos totais	sem valor de referência	2,19	2,50%	**ND**	**4,68%**	2,66%	3,19%
				146	NOVO	168		SEF	Porcentagem de variação do faturamento, em relação ao ano anterior, das empresas de bares e restaurantes	sem valor de referência	13,6%	-16,5%	**45,3%**	**36,30%**	16,70%	13,04%
				147	NOVO	169		SEF	Percentual de participação da receita de impostos do segmento de bares e restaurantes em relação aos impostos totais	sem valor de referência	0,62%	0,46%	**0,63%**	**0,80%**	0,87%	2,14%
				149	NOVO	170		SMTDI	Porcentagem de Crescimento de pessoas empregadas no segmento de tecnologia (Fonte: ACATE)	sem valor de referência	4,10%	ND	**12,22% (RAIS)**	22,15% Acate, com base em Rais (ano base 2021) e CAGED (ano base 2022)	Em Florianópolis (2022): 38.402 Crescimento de **23,49%**, na comparação com o ano anterior (31.096).	Em Florianópolis (2022): 38.402 Crescimento de 23,49%, na comparação com o ano anterior (31.096).
				150	NOVO	171		SMTDI	Porcentagem de Crescimento de pessoas empregadas no segmento de Hotelaria (Fonte: SHRBS)	sem valor de referência	ND	ND	**ND**	ND	ND	ND
				151	NOVO	172		SHRBS	Porcentagem de ocupação dos leitos de hotelaria e pousada (Fonte SHRBS)	sem valor de referência	57,80%	30,80%	**45,70%**	69,10%	57,16	63,80%
				152	NOVO	173		SMTDI	Porcentagem de Crescimento de pessoas empregadas no segmento de bares e restaurantes (Fonte: SHRBS)	sem valor de referência	3%	ND	**ND**	ND	ND	ND
				153		174	8.1.6	SMTDI /FNR	Número de empresas (por 100 mil habitantes)	sem valor de referência			**7.660**		23.440(fonte direta)	24.779

dimensões	PILAR	TEMA	SUBTEMA		ORDEM CES	NOVA ORDE	ORDEM FLORIP	ÓRGÃO RESPONSÁVEL	INDICADOR	FAIXAS PARA SEMAFORIZAÇÃO	2019	2020	2021	2022	2023	2024
	MECANISMOS ADEQUADOS DE GOVERNO	GESTÃO PÚBLICA PARTICIPATIVA	PRESTAÇÃO DE CONTAS AO CIDADÃO	154	NOVO	175		SMF	Qual a porcentagem do orçamento que a Sociedade Civil participa na sua definição	sem valor de referência	12,47	5% da arrecadação do IPTU	**5% da arrecadação IPTU**	5% do valor arrecadado do IPTU do último exercício fechado	Lei Complementar n. 756, de janeiro/2023: "5% do valor arrecadado do IPTU do último exercício fechado (2021)". 2021 era o ano que estava fechado quando a Proposta de LOA 2023 foi elaborada, em 2022.	Conforme Lei Orgâniza Municipal, a cada peça orçamentária (PPA, LDO e LOA), são realizadas pelo menos 2 (duas) audiências públicas, uma do Poder Executivo e outra dirigida pelo Poder Legislativo municipal. E se expõe a totalidade do orçcamento.
		GESTÃO PÚBLICA MODERNA	PROCESSOS MODERNOS DE GESTÃO PÚBLICA DO ORÇAMENTO MUNICIPAL	155	NOVO	176		SMF	Porcentagem do gasto com pessoal em relação ao gasto total (conforme conta 3.1.1.00.00.00 conforme dados do SICONFI do TCE-SC)	sem valor de referência	62,73%	62,63%	**55,14%**	**51,85%**	54,49%	46,07%
				156	NOVO	177		SMA	Porcentagem mensal de horas falta sem atestado, em relação ao total de horas contratadas	sem valor de referência	0,41%	0,35%	**0,50%**	**0,43%**	**0,45%**	**0,52%**
				157	NOVO	178		SMA	Porcentagem mensal de horas falta com atestado, em relação ao total de horas contratadas	sem valor de referência	9,65%	7,05%	**8,71%**	**8,32%**	**9,43%**	**10,24%**
				158	NOVO	179		SMLCP	Porcentagem do valor das compras totais da administração pública municipal feitas por meio de pregão eletrônico	sem valor de referência	28,47%	54,34%	**49,16%**	**47,75%**	43,02%	53,62%
				159	NOVO	180		SMLCP	Porcentagem do valor das compras totais da administração pública municipais feitas por meio de pregão presencial	sem valor de referência	13,30%	1,62%	**14,85%**	**4,55%**	2,22%	0,00%
				160	NOVO	181		SMLCP	Porcentagem do valor das compras totais da administração pública municipais feitas por meio de tomada de preços	sem valor de referência	17,65%	7,68%	**1,73%**	**3,26%**	6,65%	0,00%
				161	NOVO	182		SMLCP	Porcentagem do valor das compras totais da administração pública por inexigibilidade, por contratação direta	sem valor de referência	4,12%	2,27%	**3,94%**	**7,17%**	13,30%	20,55%
				162	NOVO	183		SMLCP	Porcentagem do valor das compras totais da administração pública municipais em que são dispensadas licitações com base em lei especifica	sem valor de referência	11,51%	9,83%	**16,67%**	**12,31%**	25,72%	5,85%
				163	NOVO	184		SMLCP	Porcentagem do valor das compras totais da administração pública municipal feitas por meio de concorrência pública	sem valor de referência	24,16%	18,28%	**9,50%**	**24,13%**	6,65%	13,74%

dimensões	PILAR	TEMA	SUBTEMA		ORDEM CES	NOVA ORDE	ORDEM FLORIP	ÓRGÃO RESPONSÁVEL	INDICADOR	FAIXAS PARA SEMAFORIZAÇÃO			2019	2020	2021	2022	2023	2024
FISCAL		TRANSPARÊNCIA	TRANSPARÊNCIA E AUDITORIA DA GESTÃO PÚBLICA	164	114	185		Controladoria Geral do Município	Índice de transparência: Consultar transparência internacional Brasil	> 6	3,0 - 6,0	< 3	106	ótimo	**ND**	**97,40%**	índice: 85,77% Classificação: Ouro https://radardatransparencia.atricon.org.br/radar-da-transparencia-publica.html	índice: 85,16% Classificação: Ouro https://radardatransparencia.atricon.org.br/radar-da-transparencia-publica.html
	GESTÃO ADEQUADA DA RECEITA	IMPOSTOS E AUTONOMIA FINANCEIRA	RECEITAS E IMPOSTOS MUNICIPAIS	165	118	186	9.2.6	SMF/FNR	Receita própria: Porcentagem da receita do governo municipal proveniente de tributos (tarifas, encargos e impostos) permitidos pela lei em relação à receita total.	Comparar com as metas da PMF			46,6	60%	**48%**	**55,51% no FNR informa 62,28%**	51,19%	46,85%
				166	119	187		SMF	Porcentagem das transferências totais recebidas de outros níveis de governo em relação a receita total.	Comparado com diferentes cidades - sem padrão - fazer parâmetro em SC			22,94	27,64%	**32,47%**	**34,49%**	34,05%	32,97%
				167	120	188		SMF	Porcentagem das transferências recebidas destinadas a usos específicos (pré-definidos) em relação as transferências totais	Comparado com diferentes cidades - sem padrão - fazer parâmetro em SC			49,09	12,59%	**16,56%**	**50,97%**	46,03%	56,48%
				168	121	189		SMF	Porcentagem das receitas de fontes externas ao governo municipal (excluindo-se receita própria e transferências) em relação a receita total	Comparado com diferentes cidades - sem padrão - fazer parâmetro em SC			20,3	20,45%	**18,92%**	**10,01%**	27,63%	37,37%
				169	122	190		SMF	Porcentagem das receitas próprias acrescidas as transferências sem fim definido em relação a receita total	≥ 80%	> 61% e < 80%	≤ 61%	64,7	60,19%	**64,53%**	**72,42%**	72,37%	62,63%
				170	**NOVO**	191		SMF	Porcentagem da variação anual da cota parte do ICMS	Acima do IPCA	Igual ao IPCA	Abaixo do IPCA	10,68%	0,47%	**17,86%**	**7,63%**	0,83% (IPCA 2023 = 4,62%)	12,26% (IPCA 2024 = 4,83%)
				171	**NOVO**	192		SMF	Porcentagem de variação anual da arrecadação do ISS	Acima do IPCA	Igual ao IPCA	Abaixo do IPCA	12,70%	-6,00%	**26,50%**	**30,70%**	28,37%	9,33%
				172	**NOVO**	193		SMF	Porcentagem de variação anual da arrecadação do IPTU	Acima do IPCA	Igual ao IPCA	Abaixo do IPCA	6,10%	1,31%	**9,27%**	**12,23%**	14,27%	2,09%
				173	**NOVO**	194		SMF	Percentual da variação anual da arrecadação do ITBI	Acima do IPCA	Igual ao IPCA	Abaixo do IPCA	13,01%	11,08%	**57,49%**	**-8,83%**	-4,74%	18,17%
				174	**NOVO**	195		SMF	Porcentagem de variação da dívida ativa em relação ao ano anterior	< 0	0 - IPCA	> IPCA	-0,06%	18,09%	**8,48%**	**54,78%**	105,18%	14,82%

dimensões	PILAR	TEMA	SUBTEMA		ORDEM CES	NOVA ORDE	ORDEM FLORIP	ÓRGÃO RESPONSÁVEL	INDICADOR	FAIXAS PARA SEMAFORIZAÇÃO			2019	2020	2021	2022	2023	2024
			GESTÃO DE COBRANÇAS	175	**NOVO**	196		SMF	Porcentagem de inadimplência do IPTU	sem valor de referência			38,47%	29,63%	**15,10%**	**19,77%**	19,81%	16,73%
	GESTÃO ADEQUADA DAS DESPESAS	**GESTÃO DO GASTO PÚBLICO**	QUALIDADE DO GASTO PÚBLICO	176	126	197		SMF (Siconfi-TCE/SC)	Porcentagem dos gastos correntes em relação aos gastos totais	Comparado com diferentes cidades - sem padrão - fazer parâmetro em SC			87,20%	90%	**86,70%**	**87,07%**	85,36%	86,21%
				177	127	198	9.2.5	SMF/FNR	Despesas de capital como porcentagem do total de gastos: Percentual de investimentos em ativo fixo (despesas de capital) em relação aos gastos totais	Comparado com diferentes cidades - sem padrão - fazer parâmetro em SC			12,63%	16,27%	**10,00%**	**6,82%**	14,63%	13,79%
				178	128	199		SMF	Taxa média de crescimento anual do gasto corrente: Porcentagem de variação no ano dos gastos correntes	< 0	0 - IPCA	> IPCA	38,57% (IPCA 4,30%)	(-20,35%) - (IPCA 4,51%)	**14,75% (IPCA 10,06%)**	**23,8% (IPCA 5,78%)**	**16,95% (IPCA 4,62%)**	4,46% (IPCA 4,83%)
				179	L 1	200		SMF	Despesa de pessoal/Receita corrente líquida: percentual da depesas totais (salário + encargos + vales transporte e alimentação + plano de saúde) e de pessoal em relação a receita corrente líquida	< 51,3%	51,3% a 54%	> 54%	48,51%	48,68%	**45,61%**	**45,42%**	49,53%	48,46%
				180	**NOVO**	201		SMF	Porcentagem das despesas com contratação de pessoal tercerizado (terceiros PJ + PF + locação de mão de obra) em relação a receita total líquida.	sem valor de referência			4,65%	3,33%	**4,22%**	**4,56%**	4,73%	4,20%
	Gestao Adequada da Divida	**Divida**	SUSTENTABILIDADE DA DÍVIDA	181	131	202	9.2.4	SMF/FNR	Crescimento do serviço da dívida: Porcentagem dos juros da dívida em relação a receita própria	< 5%	5% - 10%	> 10%	0,67%	0,72%	**11,00%**	**101,28% no FNR registra 8,63%**	8,55%	3,73%
				182	132	203		SMF	Crescimento da dívida: Porcentagem de crescimento da dívida (Emprestimos de curto e longo prazo)	A taxa de crescimento real anual é negativa	A taxa de crescimento real anual está entre 0% e 2%	A taxa de crescimento real anual é superior a 2%	-0,04%	-12,00%	**14,56%**	**37,74%**	-4,91%	16,94%
			LEI DE RESPONSABILIDADE FISCAL	183	L 2	204		SMF	Dívida consolidada líquida/Receita corrente líquida: Porcentagem da dívida consolidada líquida em relação a receita corrente líquida	< 50%	50% a 60%	> 60%	43,61%	36,26%	**31,82%**	**45,27%**	24,19%	34,75%
				184	L 3	205		SMF	Operação de Crédito/Receita Corrente Líquida:Porcentagem do valor das operações de crédito contratadas no ano em relação a receita corrente líquida	Menor 10%	Entre 10 e 16%	Acima 16%	6,22	6,50%	**4,00%**	**10,12%**	1,97%	5,22%

7. CONSIDERAÇÕES E RECOMENDAÇÕES :

Tomando por base os valores levantados em 2025 e sua série histórica para cada indicador, seguem abaixo as considerações e recomendações referentes aos itens que mais necessitam de atenção e providências. Deixamos de registrar comentários sobre a maioria dos aspectos em "verde" por já terem alcançado níveis satisfatórios.

7.1 Dimensão Ambiental

7.1.1. Tema: Água - 06 indicadores

a) O indicador **Consumo de Água Per Capita por Dia** é essencial para avaliar o uso sustentável dos recursos hídricos. Nos últimos cinco anos, Florianópolis apresentou uma média de **173,1 litros/pessoa/dia**, com os seguintes resultados anuais: **172,9 litros em 2020**, **163,1 litros em 2021**, **172,6 litros em 2022**, **179,9 litros em 2023** e **178,9 litros em 2024** (CASAN). Pela **semaforização atualmente aplicada**, que considera satisfatório o intervalo entre **120 e 200 litros/dia/pessoa**, o município se encontra em **condição verde**, indicando que o consumo está dentro do esperado para uma situação considerada aceitável. No entanto, quando comparado ao **referencial internacional estabelecido pela ONU**, de **110 litros/dia/pessoa** para atender adequadamente às necessidades básicas, observa-se que o consumo em Florianópolis permanece **consistentemente acima do recomendado**. Isso pode refletir tanto hábitos de uso excessivo quanto ineficiências no sistema de distribuição e perdas ao longo da rede. Embora o indicador local aponte uma situação positiva, é importante reconhecer que níveis mais altos de consumo exercem **pressão sobre os mananciais**, aumentam os custos de tratamento e distribuição e podem comprometer a sustentabilidade hídrica a longo prazo. Nesse sentido, torna-se fundamental **consolidar políticas de uso racional da água**, incentivar tecnologias de reuso e eficiência, além de reforçar campanhas de conscientização para a população.

b) O indicador de **Qualidade da Água** apresentou em **2024** o valor de **96,8%**, uma ligeira redução em relação a 2023 (97%). Esse resultado enquadra-se na **faixa amarela** (90% a 97%), que indica condição de atenção. A **média histórica dos últimos 10 anos**, de **95,44%**, também permanece dentro dessa mesma faixa, o que demonstra que, embora haja conformidade relativamente alta, o patamar não pode ser considerado plenamente satisfatório, já que sistematicamente a qualidade da água não alcança o nível mais elevado. Além disso, persiste uma lacuna significativa: a ausência de regulamentação para contaminantes por metais pesados e agrotóxicos, que não estão contemplados nos parâmetros nacionais de avaliação. Essa omissão representa um risco específico à saúde pública e ao meio ambiente, dado o efeito cumulativo e potencialmente prejudicial desses contaminantes. Assim, mesmo com índices relativamente estáveis, é fundamental avançar tanto na **elevação da conformidade** quanto na **atualização dos critérios de monitoramento**, de forma a garantir maior segurança hídrica à população.

c) A porcentagem de água não contabilizada em Florianópolis continua sendo um desafio estrutural importante. Nos últimos 10 anos (2014–2024), o índice apresentou uma média de **37,45%**, muito acima do patamar aceitável para uma gestão hídrica eficiente. Em 2023, o indicador havia registrado uma melhora para 35,87%, mas em 2024 voltou a subir para 38,09%, reforçando a oscilação e a dificuldade de manter avanços consistentes. Esse cenário reflete perdas significativas por vazamentos, ligações irregulares e problemas nos sistemas de medição, que comprometem não apenas a eficiência do abastecimento, mas também a sustentabilidade hídrica da cidade. Se essa taxa de desperdício se mantiver, a pressão sobre os recursos hídricos aumentará, especialmente diante do crescimento populacional. É fundamental que a concessionária apresente estratégias claras e consistentes para reduzir as perdas, seja por investimentos em tecnologia, manutenção preventiva ou modernização da rede, assegurando que a água tratada chegue de forma plena e sustentável à população.

d) É extremamente preocupante constatar que, desde **2019**, não recebemos informações sobre o indicador **"Número remanescente de anos de saldo hídrico positivo"**, conforme os parâmetros solicitados. Trata-se de uma métrica estratégica, que reflete a capacidade de uma região em manter o equilíbrio sustentável no ciclo da água e, portanto, é essencial para o planejamento e para a tomada de decisões que afetam diretamente a vida das comunidades e o desenvolvimento do território. A ausência sistemática desses dados há cinco anos compromete a possibilidade de avaliar riscos futuros e adotar medidas preventivas eficazes. O saldo hídrico positivo não é apenas um dado técnico: ele representa a garantia de acesso à água potável, a preservação dos ecossistemas aquáticos, a segurança alimentar e até a estabilidade econômica em regiões que dependem da agricultura. A água é um recurso finito e essencial para a vida, e é responsabilidade de todos nós, em especial dos gestores públicos, garantir que ela seja gerenciada de forma responsável e eficaz para as gerações presentes e futuras.

A análise dos indicadores relacionados à água em Florianópolis evidencia que os desafios persistem e que as recomendações dos relatórios anteriores ainda não se traduziram em melhorias significativas. O consumo per capita segue acima dos parâmetros de referência internacionais, as perdas por água não contabilizada permanecem em níveis críticos, e o indicador de qualidade da água tem se mantido majoritariamente na faixa de atenção, sem alcançar de forma consistente o patamar considerado ideal. Além disso, desde 2019 não há divulgação do indicador "Número remanescente de anos de saldo hídrico positivo", o que representa uma lacuna grave no planejamento.

Diante desse cenário, é fundamental que tanto a Prefeitura de Florianópolis quanto a CASAN adotem ações mais efetivas de gestão hídrica, com foco na redução de perdas, uso eficiente, monitoramento mais rigoroso da qualidade e transparência na divulgação de dados. Sem avanços concretos nessas frentes, a cidade corre o risco de comprometer a segurança hídrica da população e a sustentabilidade de seus recursos no médio e longo prazo.

7.1.2. Tema: Saneamento e Drenagem – 03 indicadores

a) O **índice de cobertura de ligações de moradias ao sistema de esgotamento sanitário** em Florianópolis permanece em um patamar crítico. Em **2024, o percentual caiu para 64,81%**, representando mais um retrocesso em relação a 2023 (66,67%) e consolidando uma tendência preocupante de queda nos últimos anos. Ao observar a série histórica de 2014 a 2024, verifica-se uma evolução inicial — de 45% em 2014 para 68,89% em 2021 —, seguida por um período de estagnação e, mais recentemente, de regressão, com a taxa recuando para níveis abaixo de 2018. Essa trajetória indica não apenas a dificuldade da cidade em ampliar a cobertura de esgoto, mas também a perda de avanços conquistados em anos anteriores. Esse cenário revela um desafio estrutural grave: Florianópolis não tem conseguido acompanhar o crescimento populacional com investimentos proporcionais em infraestrutura de saneamento. A insuficiência de cobertura compromete tanto a saúde pública quanto a preservação ambiental, especialmente em uma cidade que depende da qualidade de seus recursos naturais para sustentar o turismo e a qualidade de vida da população. Para reverter esse quadro, é imprescindível que as autoridades municipais e estaduais assumam o saneamento básico como prioridade, garantindo investimentos contínuos, planejamento integrado e transparência na execução. Sem medidas efetivas, a cidade corre o risco de aprofundar desigualdades urbanas e comprometer sua sustentabilidade no longo prazo.

b) O indicador de **tratamento de águas residuais** em Florianópolis apresentou oscilações importantes na última década, variando de 51% a 65,07% entre 2014 e 2024. Em **2024, registrou 63,15%**, uma melhora em relação ao resultado de 2023 (60,14%) e suficiente para mantê-lo na faixa verde da semaforização (> 60%). Esse avanço em relação ao ano anterior é encorajador e pode sinalizar uma retomada positiva após o período de quedas consecutivas observado desde 2021. Entretanto, o histórico revela fragilidade e falta de consistência, uma vez que o indicador já esteve próximo do limite inferior da faixa verde. Para consolidar uma trajetória de crescimento estável, é fundamental que sejam aprofundadas as ações de investimento em infraestrutura, modernização tecnológica e gestão operacional. Garantir a melhoria contínua nesse indicador é essencial tanto para a preservação ambiental quanto para a saúde pública, além de estar diretamente ligado ao cumprimento das metas de saneamento e sustentabilidade urbana.

c) O indicador de **moradias afetadas por inundações intensas** em Florianópolis vem apresentando uma trajetória de crescimento extremamente preocupante. Desde 2018, os resultados evoluíram de 0,5% para **15% em 2024**, ultrapassando em muito o limite vermelho da semaforização (> 3%). Essa tendência de alta contínua evidencia o agravamento dos impactos tanto do transbordamento de sistemas de drenagem e esgoto quanto de enchentes provocadas por rios e marés. As causas possíveis incluem deficiências na manutenção e na capacidade dos sistemas de drenagem, agravadas por fatores como a

urbanização desordenada, a impermeabilização do solo e a elevação do nível do mar. Esse cenário exige **investimentos urgentes em infraestrutura resiliente**, aliando medidas de prevenção, planejamento urbano e adaptação climática. Essa situação exige investimentos em infraestrutura resiliente e medidas preventivas robustas para mitigar os efeitos dessas inundações. Adicionalmente, é essencial promover a conscientização pública sobre práticas de segurança e planejamento urbano que possam ajudar a reduzir os impactos desses eventos extremos. Uma gestão hídrica sustentável e o fortalecimento da infraestrutura de drenagem são fundamentais para conter o avanço desse problema e proteger as comunidades vulneráveis. A análise constante dos dados e a implementação de medidas corretivas imediatas são essenciais para reverter essa tendência negativa e garantir a segurança das áreas mais afetadas.

d) Entendemos que o investimento em Saneamento e Drenagem transcende a simples infraestrutura; é uma estratégia essencial para o desenvolvimento sustentável de Florianópolis, assegurando que a cidade continue a atrair visitantes e que seus habitantes usufruam de uma melhor qualidade de vida.

e) Como o novo Plano Diretor permite a venda de potencial construtivo, é importante a gestão adequada das compensações, a exemplo de melhorias na mobilidade e drenagem.

f) Observamos, também, que o tema saneamento se consolidou como um movimento social significativo, com expressiva mobilização por parte de cidadãos, profissionais e entidades. Esses grupos têm demonstrado crescente insatisfação com a concessão à Casan, questionando a gestão de um recurso tão fundamental para a saúde pública e para a qualidade de vida urbana.

g) O saneamento é reconhecido como um tema prioritário e urgente, um problema a ser resolvido com máxima rapidez. Acreditamos que as discussões e reivindicações em torno dessa questão continuarão a impulsionar melhorias, seja em termos de novas políticas, mudanças de gestão ou avanços concretos na eficiência desse serviço.

h) Para assegurar um progresso contínuo e consistente, sugerimos que sejam implementados mecanismos de transparência e engajamento permanente entre a concessionária, o governo e a sociedade civil. Relatórios públicos regulares e dados acessíveis sobre os avanços e desafios podem manter a população informada e participativa, fortalecendo o acompanhamento das soluções e garantindo que Florianópolis consiga concretizar as transformações que tanto necessita.

7.1.3 Tema: Gestão de Resíduos Sólidos – 08 indicadores

a) De acordo com o Banco Mundial, a média global de produção de **resíduos sólidos urbanos** é de aproximadamente 0,74 kg **por pessoa por dia**. Isso significa uma média anual de cerca de 270 kg por pessoa. Esses números podem variar dependendo do país e do contexto específico. Em Florianópolis, o indicador mostra uma oscilação preocupante ao longo dos últimos anos. Desde 2018, os resultados foram: **2,32 kg/hab/dia; 1,16;**

1,10; 1,05; 1,09; 1,28 e 1,14 em 2024. Embora os valores tenham se mantido na **faixa amarela de semaforização** (1,01 a 1,5 kg/hab/dia) desde 2019, o patamar atual ainda está significativamente acima da média global de referência. Em 2024, o consumo foi de **1,14 kg/hab/dia**, o que corresponde a aproximadamente **416 kg de resíduos por pessoa ao ano** – mais de 50% superior à média mundial. Essa situação reforça a necessidade de estratégias consistentes para **reduzir a geração de resíduos na fonte**, estimulando práticas de **consumo consciente, reutilização, reciclagem e compostagem**. Além disso, políticas públicas mais efetivas de gestão integrada de resíduos sólidos, aliadas à **conscientização da população**, são essenciais para que Florianópolis avance em direção a padrões mais sustentáveis e compatíveis com a preservação ambiental.

b) A análise dos dados mais recentes mostra uma tendência positiva na redução da **porcentagem de resíduos sólidos municipais destinados a aterros sanitários**. O percentual, que estava em 93,27% em 2021, caiu para 88,82% em 2022, 86,38% em 2023 e se manteve em um patamar similar em 86,81% em 2024. Apesar da leve melhora, a situação ainda é preocupante. O índice permanece muito acima do patamar de menos de 35%, que seria considerado ideal para a sustentabilidade. A alta dependência de aterros sanitários é agravada pelo fato de Florianópolis não ter uma estrutura própria, destinando a maioria de seus resíduos para o aterro de Biguaçu. Essa logística de transporte de longa distância não só aumenta significativamente os custos de gestão, mas também eleva a pegada de carbono da operação. A boa notícia é que o percentual de resíduos compostados pela Prefeitura de Florianópolis deu um salto notável. Depois de subir de 0,91% em 2021 para 4,56% em 2023, a porcentagem atingiu 12,93% em 2024. Esse aumento demonstra que as políticas e programas de compostagem estão começando a gerar resultados expressivos, aproximando a cidade da meta ideal de 20%. É crucial fortalecer as políticas públicas e os programas de conscientização para incentivar a participação da população. A melhoria contínua desse indicador não apenas contribuirá para a preservação ambiental e a saúde pública, mas também resultará em economia de recursos e na redução dos impactos negativos das atividades humanas no planeta. A destinação dos resíduos para fora da cidade ressalta ainda mais a urgência de reduzir a quantidade de lixo gerado na fonte.

c) A trajetória de **reciclagem** em Florianópolis tem mostrado um crescimento constante nos últimos anos. Em **2024**, a cidade alcançou um novo patamar, com **10,73%** dos resíduos sólidos separados e classificados para reciclagem. Esse resultado demonstra uma evolução positiva, especialmente se comparado aos **3,76%** de 2021. No entanto, é crucial reconhecer que, apesar do avanço, a porcentagem ainda se encontra na faixa vermelha do sistema de semaforização (abaixo de 15%). Isso indica que a cidade ainda está a uma distância considerável do parâmetro considerado ideal, que é de 25% ou mais. A melhoria contínua desse indicador parece ser impulsionada em grande parte por um amadurecimento e uma crescente conscientização da própria

população. Para que esse movimento se acelere e a cidade atinja patamares mais sustentáveis, é fundamental que as políticas públicas acompanhem esse ritmo. O fortalecimento das parcerias com entidades de reciclagem e aprimoramento da infraestrutura de coleta seletiva são essenciais. Além disso, a prefeitura pode ampliar a divulgação dos resultados e investir em campanhas mais visíveis e eficazes, transformando o engajamento natural da população em uma ação coletiva e coordenada. Ao alinhar a conscientização da comunidade com ações estratégicas de gestão de resíduos, Florianópolis poderá se aproximar de padrões mais eficientes e se consolidar como uma cidade verdadeiramente sustentável. .

d) Em 2024, a situação referente ao **aproveitamento de resíduos sólidos para geração de energia** em Florianópolis permanece inalterada, com o indicador em 0%. Essa ausência de avanço reflete não apenas a falta de iniciativas, mas também a complexidade de se implementar soluções que possam entrar em conflito com o perfil da cidade. A forte vocação de Florianópolis para o turismo, serviços e a chamada "economia limpa" cria barreiras e resistência social e política a projetos que possam ser associados a grandes estruturas industriais. Em um cenário de custos crescentes de energia e de urgência em reduzir o volume de resíduos em aterros, essa inércia representa uma oportunidade perdida para a cidade, especialmente considerando que a logística de destinação do lixo já é um grande desafio. O aproveitamento energético poderia não apenas reduzir os custos operacionais, mas também mitigar a poluição. Para que Florianópolis avance em direção a uma gestão de resíduos mais eficiente e sustentável, é fundamental que as autoridades considerem soluções que se alinhem ao perfil da cidade. Isso pode envolver a busca por tecnologias mais modernas, de menor impacto visual e ambiental, ou modelos descentralizados. Encontrar um caminho que transforme o resíduo em um recurso energético de forma limpa e compatível com sua identidade é o passo crucial para a sustentabilidade a longo prazo.

e) É imperativo que Florianópolis adote uma abordagem proativa e inovadora em relação à gestão de resíduos sólidos. A implementação de estratégias eficazes para aumentar a coleta seletiva, a reciclagem e o tratamento de resíduos orgânicos não é apenas uma responsabilidade ambiental, mas também uma oportunidade de transformar a cidade em um modelo de sustentabilidade. A sensibilização da população e o fortalecimento das parcerias com entidades locais são fundamentais para criar uma cultura de responsabilidade coletiva em relação aos resíduos. Além disso, a exploração de tecnologias de valorização de resíduos, como a conversão em energia, deve ser uma prioridade. Ao agir de forma decisiva agora, Florianópolis pode não apenas avançar em direção à sua meta de Lixo Zero, mas também garantir um futuro mais saudável e sustentável para seus cidadãos e o meio ambiente.

7.1.4 Tema: Energia – 06 indicadores

a) A quantidade anual de horas de interrupções elétricas por cliente em Florianópolis manteve-se em um patamar satisfatório em 2024, com uma média de **5,61 h/domicílio/ano**. Esse resultado continua na faixa **verde** do sistema de semaforização, que considera aceitáveis médias inferiores a 7 horas. Apesar da leve alta em relação a 2023 (5,45 h/domicílio/ano), o valor de 2024 demonstra a estabilidade da rede após a significativa elevação para 7,24 horas em 2021. Desde então, a cidade tem mantido o indicador abaixo do limite de alerta, o que reflete a resiliência do sistema e os esforços para garantir a qualidade do fornecimento de energia. A média dos últimos seis anos (5,66 h/domicílio/ano) confirma que, apesar de flutuações pontuais, o serviço de distribuição de energia na capital tem se mantido dentro de padrões satisfatórios. No entanto, é fundamental que a concessionária e as autoridades continuem a investir em manutenção e modernização da infraestrutura. A atenção contínua é essencial para prevenir novas instabilidades e assegurar que o fornecimento de energia continue confiável para a população, apoiando o desenvolvimento econômico e a qualidade de vida da cidade.

b) Florianópolis deu um salto impressionante na modernização de sua iluminação pública, alcançando um marco notável em 2024. A porcentagem de luminárias LED instaladas subiu de 45% em 2023 para expressivos **77%** em 2024, representando um total de **44.660 luminárias**. Esse resultado extraordinário coloca a cidade na faixa **verde** do sistema de semaforização, superando a meta de 50%. O avanço é particularmente significativo se comparado ao ritmo lento de crescimento observado nos anos anteriores, quando a cidade lutava para sair da faixa vermelha. A transição para a iluminação LED é uma conquista em múltiplas frentes. Além de reduzir o consumo de energia e os custos de manutenção para o município, a tecnologia melhora a segurança e a qualidade de vida da população. É um passo fundamental em direção a uma cidade mais inteligente e sustentável. Agora, o foco deve ser na conclusão da substituição das luminárias restantes para atingir 100% de cobertura, garantindo a manutenção e a eficiência de todo o sistema.

c) A porcentagem de energia proveniente de fontes renováveis em Florianópolis continua a apresentar um cenário de grande volatilidade. Em 2024, o indicador registrou **3,88%**, representando uma leve melhora em relação aos 1,95% dos dois anos anteriores, mas ainda muito distante do patamar ideal. O resultado de 2024 mantém a cidade na faixa **vermelha**, reforçando a necessidade urgente de políticas e investimentos mais consistentes. O pico de 26,70% em 2021, que colocou a cidade na faixa amarela, provou ser uma exceção, seguido por uma queda brusca. A lenta recuperação observada em 2024 evidencia a falta de uma estratégia de longo prazo para acelerar a transição

energética. Para alcançar um futuro mais sustentável e cumprir a meta ambiciosa de **mais de 50%** de energia de fontes renováveis, é fundamental que a cidade vá além de iniciativas pontuais. É preciso um compromisso sério e contínuo com a implementação de tecnologias limpas e o fomento à geração distribuída. A estabilidade do indicador em patamares baixos sublinha o tamanho do desafio e a importância de que a busca por uma matriz energética mais limpa se torne uma prioridade inegociável.

7.1.5 Tema: Qualidade do Ar – 02 indicadores

A situação do **monitoramento da qualidade do ar** em Florianópolis permanece inalterada em 2024, representando uma lacuna crítica na gestão ambiental em relação aos dados fundamentais sobre a qualidade do ar que se respira.

A única referência de dados disponíveis para a cidade é o registro de 2014, quando a concentração de Material Particulado (MP) 10 foi de 23 $\mu g/m^3$, um índice satisfatório na época. Contudo, essa informação já obsoleta o que não necessariamente reflete a realidade atual, que pode ser impactada pelo crescimento da frota de veículos, atividades da construção civil e outros fatores.

A ausência de um monitoramento contínuo impede que o poder público identifique proativamente os riscos ambientais. E, igualmente importante, a falta de acesso à informação de qualidade impede que a população compreenda os riscos à sua própria saúde pública e exija políticas mais eficazes. Para preencher essa lacuna, é fundamental que a cidade estabeleça parcerias estratégicas com universidades e institutos de pesquisa. A implementação de um sistema de monitoramento consistente é o primeiro e mais importante passo para garantir que os dados não apenas sejam coletados, mas também disponibilizados de forma transparente e acessível para todos os cidadãos.

7.1.6 Tema: Mitigação das mudanças climáticas – 01 indicador

A falta de dados para 2024 referente às **emissões de GEE** de Florianópolis confirma a preocupação levantada nos relatórios anteriores: a coleta de informações sobre este indicador é intermitente e carece de consistência. Sem a atualização para o ano mais recente, não é possível avaliar se a significativa redução para **1,74 toneladas per capita**, registrada em 2023, reflete uma tendência sustentável ou foi apenas uma variação pontual.

Essa lacuna no monitoramento impede uma análise precisa do impacto das políticas públicas de mitigação das mudanças climáticas. Desde 2014, os registros têm sido irregulares e, em alguns casos, questionáveis pela sua uniformidade. A ausência de dados para 2024 é um indicativo claro de que o problema persiste e que o sistema de monitoramento não está alinhado com a urgência do tema.

Para que Florianópolis possa, de fato, planejar e implementar estratégias eficazes contra o aquecimento global, é fundamental que as autoridades, como a Floram, estabeleçam um sistema de **monitoramento contínuo e preciso**. Apenas com dados confiáveis e atualizados será possível avaliar o real progresso da cidade, justificar investimentos e tomar decisões baseadas em evidências para um futuro mais verde e resiliente.

7.1.7 Tema: Ruído – 01 indicador

O indicador de **ruído nos principais pontos críticos** de Florianópolis revela uma lacuna de monitoramento ainda mais profunda do que a simples ausência de dados anuais. Conforme informações da fonte, **desde 2019, quando o indicador foi incluído no acompanhamento, a estrutura de medição e análise nunca foi implementada**. Isso significa que, há cinco anos, a cidade opera sem a capacidade de avaliar, de forma consistente, os níveis de poluição sonora.

Essa falha sistêmica impede que a Prefeitura e a sociedade em geral tenham acesso a informações essenciais para a saúde pública e o planejamento urbano. Sem dados, é impossível identificar áreas críticas, entender os impactos do ruído no bem-estar da população e desenvolver políticas públicas eficazes, como ações de controle de tráfego e zoneamento.

A ausência de um sistema de monitoramento não é apenas um problema de dados, mas um obstáculo fundamental para uma gestão urbana de qualidade. É crucial que as autoridades reconheçam essa falha e tomem medidas imediatas para criar a infraestrutura necessária para o acompanhamento do ruído. A implementação desse sistema não é uma opção, mas uma etapa fundamental para a garantia de um ambiente mais saudável e habitável para todos os cidadãos de Florianópolis.

7.1.8 Tema: Vulnerabilidade Frente aos Desastres Naturais no Contexto das Mudanças Climáticas – 05 indicadores

a) Em 2024, a cidade de Florianópolis manteve-se na faixa **verde** do indicador, com 90% das **áreas de risco mapeadas**. Este é um resultado positivo que demonstra o compromisso contínuo com a segurança e o planejamento urbano. No entanto, a pequena queda em

relação aos anos anteriores, quando o mapeamento atingiu **100%** de cobertura de 2019 a 2023, acende um sinal de alerta. Embora o resultado de **90%** ainda seja considerado satisfatório, a redução de dez pontos percentuais levanta questionamentos. É fundamental que as autoridades identifiquem a causa dessa diminuição, seja por mudanças na metodologia, o surgimento de novas áreas de risco não mapeadas ou a descontinuidade de monitoramento em regiões já conhecidas. Para garantir que a cidade mantenha um alto nível de preparação e resiliência, é crucial investigar essa variação e trabalhar para retornar a uma cobertura de 100%. A segurança da população depende de um monitoramento abrangente e preciso, sem margem para lacunas.

b) O **orçamento de Florianópolis destinado à mitigação de riscos de desastres naturais** apresentou uma queda preocupante em 2024. A porcentagem alocada foi de apenas **0,07%**, o que representa uma redução significativa em relação aos anos anteriores e coloca o indicador em um de seus patamares mais baixos desde 2020. Analisando a série histórica, observa-se que o orçamento tem se mantido na faixa **vermelha** (abaixo de 0,3%) desde 2020. Enquanto houve um pequeno aumento progressivo entre 2020 e 2022, o valor de 2024 representa um retrocesso, distanciando a cidade ainda mais do percentual ideal de **mais de 0,5%** necessário para a condição verde. Essa falta de priorização orçamentária para a prevenção e resposta a desastres naturais é alarmante, especialmente no contexto de um clima cada vez mais instável. O baixo nível de investimento compromete a capacidade da cidade de se tornar mais resiliente e segura. É crucial que a administração pública reveja a alocação de recursos, pois o aumento de verbas nessa área é fundamental para proteger vidas e a infraestrutura urbana a longo prazo.

c) O indicador que acompanha o **número de edificações em áreas de risco** em Florianópolis continua a apresentar um crescimento alarmante. Em 2024, o número de unidades registradas subiu para **2.100**, uma elevação significativa em relação às **1.593** de 2023 e às **1.080** de 2022. Essa tendência de aumento constante e acentuado, mesmo sem uma série histórica mais ampla, já é um sinal de alerta grave. O crescimento de edificações em locais suscetíveis a deslizamentos e inundações indica um desafio cada vez maior para a segurança e a resiliência da cidade. A ausência de um parâmetro de semaforização não diminui a urgência da situação. A progressão de **1.080 para 2.100** unidades em apenas dois anos aponta para uma expansão descontrolada de ocupações em áreas de risco. É fundamental que as autoridades de Florianópolis intensifiquem as estratégias de fiscalização, prevenção e, quando necessário, de realocação de famílias, para mitigar os perigos e proteger a vida dos cidadãos.

7.2. Dimensão Urbana

Florianópolis (Plano de Ação Florianópolis Sustentável 2014 - https://issuu.com/ciudadesemergentesysostenibles/docs/florianopolissustentavel; acessado em 14/11/2024) definiu como estratégia de ação a busca da garantia da sustentabilidade urbana, isto é, pensar permanentemente a relação entre o ambiente natural e o ambiente construído. Para tanto é necessário um planejamento estruturado de forma a atacar as vulnerabilidades, bem como preparar o Município para as mudanças, gerenciando a expansão da urbanização e evitando a expansão predatória sobre seus recursos ativos ambientais. Isso implica organizar o seu território, implementar mecanismos de integração de políticas públicas de criação de oportunidades de desenvolvimento qualitativo de vida de sua população residente, imigrantes e visitantes temporários. Ora o estado de cada indicador revela o avanço das ações planejadas ou não. Cada vez mais fica evidenciado a importância do fortalecimento da solidariedade e cooperação entre todos os Agentes da Sociedade para a complementação das ações e resultados positivos esperados ou preconizados. A solidariedade e cooperação não pode ser só um traço entre indivíduos, grupos ou lugares, mas especialmente com a natureza, aspecto especial marcante no caso de Florianópolis que protege praticamente 60% do seu território como Áreas de Preservação Permanente, verdadeiro capital natural de intensas trocas com o espaço social construído.

A sustentabilidade ambiental, econômica e social vem ganhando contornos positivos crescentes, consequentemente gerando padrões mais elevados de vida para seus habitantes, destacando-se como uma cidade muito atrativa no cenário nacional. Há muitas questões preocupantes, mas algumas fizeram parte das discussões da revisão do Plano Diretor como a expansão urbana, densidade, verticalização, centralidades, mobilidade, orla marítima, habitação, ... A falta de informações sistemáticas como a expansão da malha urbana, densidade urbana, déficit habitacional, etc em 2023 e 2024 prejudica o processo de análise e visualização do desenvolvimento de Florianópolis. Resta-nos o pedido insistente de fornecimento desses dados para a garantia das informações necessárias para a sociedade florianopolitana.

7.2.1 Tema: Uso do Solo e Ordenamento Territorial – 11 indicadores

A) O indicador de **crescimento da malha urbana de Florianópolis** continua a apresentar um desempenho positivo e consistente. Em 2024, a expansão da malha viária foi de **1,41%**, mantendo o percentual na faixa **verde** do sistema de semaforização, que estabelece o limite de 3% ao ano para um crescimento saudável e planejado. Analisando a série histórica disponível, é evidente que a cidade tem conseguido manter o seu desenvolvimento dentro de um ritmo sustentável desde 2019. Os dados mostram uma flutuação controlada, mas sempre abaixo do limite de alerta. A ausência de um registro para 2023 não impede a análise de uma tendência de crescimento que, apesar da expansão, se mantém alinhada com os princípios de um planejamento urbano consciente e voltado à sustentabilidade.Esse resultado é um sinal

positivo de que Florianópolis está conseguindo conciliar seu desenvolvimento com a necessidade de preservar sua qualidade de vida e o meio ambiente natural. A manutenção desse padrão é fundamental para garantir que o crescimento da cidade ocorra de forma ordenada e benéfica para todos os cidadãos.

B) A análise do **crescimento demográfico de Florianópolis** em 2024 apresenta um desafio devido à falta de dados fornecidos pela fonte oficial da Prefeitura Municipal de Florianópolis (PMF). No entanto, com base em projeções e estimativas de fontes confiáveis como o **IBGE**, foi possível obter uma visão atualizada e crucial sobre a dinâmica populacional da cidade.Os dados mais recentes indicam que a população de Florianópolis alcançou aproximadamente **576 mil habitantes em 2024**, com projeções apontando para cerca de **587,5 mil** em 2025. Esse crescimento representa um aumento anual de aproximadamente **1,9%**. Embora inferior ao pico atípico de 4,01% registrado em 2022, esse percentual ainda coloca o crescimento demográfico na faixa **vermelha** (acima de 1,5% ao ano), confirmando que a cidade mantém um ritmo de expansão acelerado. Essa rápida elevação na densidade populacional intensifica a pressão sobre a infraestrutura urbana, os serviços públicos e o meio ambiente. O aumento da população exige uma gestão mais estratégica do espaço urbano e um planejamento que garanta o equilíbrio entre a expansão da cidade e a preservação de sua qualidade de vida. O monitoramento contínuo e preciso desses indicadores é fundamental para que as políticas públicas possam responder de forma eficaz aos desafios e oportunidades que o crescimento acelerado impõe.

C) O indicador de **densidade populacional por área urbanizada** continua a apresentar um aumento significativo. Embora a fonte oficial não tenha fornecido dados para 2023 e 2024, a projeção baseada na população do Censo de 2022 e nas estimativas mais recentes do IBGE revela um crescimento contínuo. A densidade, que em 2022 era de **5.113,88 hab/km²**, é estimada em **5.300,22 hab/km² em 2023** e atinge **5.486,56 hab/km² em 2024**. Esse aumento progressivo da densidade, que se mantém em um ritmo acelerado, reforça as conclusões sobre a necessidade de um planejamento urbano eficaz. Uma maior concentração de pessoas em uma área limitada gera desafios relacionados ao congestionamento, à pressão sobre a infraestrutura e à demanda por serviços públicos de qualidade. É crucial que as autoridades municipais utilizem esses dados e projeções para adotar medidas que garantam um desenvolvimento urbano ordenado. O monitoramento preciso da densidade populacional é essencial para assegurar que o crescimento da cidade não comprometa a qualidade de vida dos cidadãos e a sustentabilidade ambiental.

D) A análise da **porcentagem de moradias de Florianópolis que não respeitam os padrões de habitabilidade** enfrenta uma lacuna de dados alarmante. Conforme informações da fonte, o último registro

oficial para este indicador é de **2019**, quando o percentual era de **2,52%**. A ausência de monitoramento sistemático desde então impede qualquer avaliação sobre a situação atual e representa um obstáculo para a gestão pública. No entanto, um relatório oficial mais recente lança luz sobre a gravidade do problema habitacional. O **"Estudo Sobre o Déficit Habitacional de Florianópolis" (agosto de 2023)**, de autoria do município, indicou que **6.163 famílias** inscritas no CadÚnico não possuem moradia adequada. Esse número representa **15%** das famílias analisadas, um dado muito superior ao último registro oficial disponível e que evidencia que a cidade enfrenta um desafio habitacional muito maior do que o historicamente monitorado.

E) A análise do **déficit habitacional quantitativo** em Florianópolis está comprometida pela falta de informações. A fonte não disponibilizou dados para 2024, o que impede qualquer avaliação sobre a evolução de um dos indicadores sociais mais críticos da cidade.

F) Os últimos dados disponíveis, de 2022 e 2023, já pintam um quadro alarmante, com um déficit de **21.705 famílias**, o que representa **52%** do total de famílias cadastradas no CadÚnico. Esse percentual está muito acima do limite de **20%** que estabelece a condição vermelha, sinalizando um grave problema de acesso à moradia. A ausência de dados para 2024, em particular, impossibilita saber se o cenário se agravou, se estabilizou ou se as políticas do novo Plano Diretor, que têm a moradia como ponto central, começaram a gerar resultados.Essa lacuna na coleta de informações demonstra a falta de um sistema de monitoramento eficaz e compromete a capacidade da Prefeitura de gerir e mensurar a eficácia de suas políticas. Para que o compromisso com a redução do déficit habitacional se traduza em ações efetivas, é crucial que a cidade priorize a coleta de dados de forma contínua e confiável. A transparência e a disponibilidade desses dados são fundamentais para que o poder público e a sociedade possam acompanhar o progresso e garantir que a população em vulnerabilidade social tenha acesso a moradias dignas.

G) A falta de informações sobre o percentual de edificações em áreas de conflito ambiental se tornou um problema crônico em Florianópolis. Pelo segundo ano consecutivo, a fonte não disponibilizou dados para 2023 e 2024, criando uma lacuna de monitoramento que impede a análise e a definição de ações eficazes. Os últimos dados disponíveis, de 2019 a 2022, já indicavam um cenário preocupante. Com percentuais que variaram entre **9,24% e 10,65%**, o indicador se manteve em uma situação de alerta máximo, bem acima do limite de **2%** que o enquadra na faixa **vermelha**. Essa tendência histórica de ocupação irregular em áreas de risco ambiental, combinada com a ausência de monitoramento atual, é um fator de grande preocupação. Essa falta de informações não apenas demonstra a incapacidade do poder público em mensurar a dimensão do problema, mas também impede a avaliação do impacto de iniciativas como o projeto REURB. É fundamental que a

cidade rompa com essa inércia e estabeleça um sistema de monitoramento contínuo e transparente. A falta de dados pode levar a uma percepção de que o problema foi negligenciado, comprometendo a credibilidade e a eficácia das políticas de gestão territorial e ambiental.

H) A análise da gestão ambiental em Florianópolis revela um paradoxo preocupante. A cidade se destaca por seu **capital natural**, com vastas áreas protegidas sob legislações federais, estaduais e municipais, formando um verdadeiro mosaico de conservação. Exemplos notáveis incluem o Parque Nacional da Serra do Tabuleiro, o Parque Estadual do Rio Vermelho e a Área de Proteção Ambiental (APA) de Santo Antônio de Lisboa, além das 10 Unidades de Conservação (UCs) de gestão municipal. No entanto, a eficácia da proteção dessas áreas está em sério risco. O indicador de **UCs com plano de manejo**, que é fundamental para a gestão e fiscalização, registrou uma queda alarmante. Em 2024, apenas **20%** das UCs municipais tinham seu plano de manejo, uma redução drástica em relação aos **41,6%** de 2022. Essa queda representa um retrocesso significativo, distanciando a cidade da meta desejável de mais de 95%. A falta de planos de manejo adequados compromete a integridade dessas áreas protegidas e agrava problemas já existentes, como a ocupação irregular do solo. Embora o percentual de áreas parceladas com irregularidades tenha se mantido estável em torno de **37,89%** em 2024, a ausência de um plano de gestão robusto para as UCs dificulta o combate a novas irregularidades. O novo Plano Diretor aprovado na Câmara é um instrumento fundamental para o ordenamento territorial. No entanto, sua eficácia depende da sua capacidade de ser colocado em prática, o que, no caso das áreas protegidas, requer a conclusão urgente dos planos de manejo para garantir a segurança e a preservação do inestimável patrimônio natural de Florianópolis.

7. 2.2 Tema: Desigualdade Urbana – 07 indicadores

Esse tema tem uma importância significativa porque mede a qualidade de vida no processo de urbanização nos diferentes segmentos sociais da cidade.

A) A análise dos indicadores de pobreza e desigualdade em Florianópolis para 2024 traz um cenário com avanços notáveis, embora desafios persistam. A cidade continua a se destacar no contexto nacional, reforçando sua posição como um local com melhores condições sociais. Os dados mais recentes da PNAD Contínua (2023) indicam que a **porcentagem da população de Florianópolis vivendo abaixo da linha internacional de pobreza** é de **4,8%**. Esse número representa uma melhoria em relação aos 5,27% registrados em anos anteriores. A informação sobre a **linha nacional de pobreza** se mantém em **4,81%** (repetindo o dado de 2023). Embora a situação da capital seja

muito superior à média nacional (29,6%) e estadual (10,16%), é importante notar que o patamar atual ainda é significativamente mais alto que o registrado no Censo de 2010, quando a taxa era de apenas 1,35%. Isso evidencia que, apesar dos avanços, o combate à pobreza ainda exige atenção contínua. O indicador que mede a concentração de renda em Florianópolis alcançou uma marca histórica. Com o registro de **0,4** no **Coeficiente de Gini** (dados IBGE 2023), a cidade atingiu a condição de **situação satisfatória**, conforme estabelecido para este relatório. Essa marca representa um avanço significativo em relação ao 0,41% de 2022 e 0,54% de 2010. A redução da desigualdade de renda é uma das maiores conquistas da cidade neste período, demonstrando que políticas e dinâmicas econômicas estão contribuindo para uma distribuição de renda mais equitativa. Em resumo, a cidade celebra a conquista de ter alcançado um patamar satisfatório na redução da desigualdade. No entanto, o desafio de diminuir o percentual da população abaixo da linha de pobreza, que ainda está acima dos níveis históricos, deve permanecer como uma prioridade na agenda de políticas públicas.

B) A análise da remuneração média dos trabalhadores formais em Florianópolis continua comprometida pela falta de dados atualizados. A fonte responsável pelo seu relatório não disponibilizou informações para 2023 e 2024, criando uma lacuna que impede o monitoramento em tempo real da saúde econômica da cidade. No entanto, com base em fontes de dados públicas e oficiais, podemos atualizar a análise até o ano mais recente com informações consolidadas.

- **Dados da RAIS (Ministério do Trabalho e Emprego)**: O conjunto de dados completo mais recente da RAIS, divulgado em 2023, aponta para o ano de 2022. Conforme essa fonte, a remuneração média dos trabalhadores formais em Florianópolis subiu para **R$ 5.867,14**, o que representa um aumento em relação ao salário de R$ 5.459,98 (RAIS 2021) do ano anterior.

A ausência de informações para os anos de 2023 e 2024, no entanto, reforça a necessidade de um sistema de coleta de dados mais ágil e consistente. Sem ele, a capacidade da cidade de entender as desigualdades urbanas, planejar políticas econômicas e avaliar a qualidade de vida da população em tempo real fica significativamente limitada.

7. 2.3 Tema: Mobilidade e Transporte – 23 indicadores.

A mobilidade e o transporte em Florianópolis continuam a ser um dos desafios mais urgentes da cidade, afetando a rotina de moradores e o fluxo de turistas. A complexidade do problema abrange desde a **infraestrutura viária** limitada, que cria pontos de **congestionamento** crônico, até a falta de um sistema

integrado de modais, que poderia desafogar as vias e oferecer alternativas ao uso massivo do carro particular.

A geografia única da cidade, com suas pontes e a divisão entre ilha e continente, amplifica as dificuldades, evidenciando a necessidade de um **planejamento regional** que vá além dos limites municipais. Há um consenso de que a solução para os gargalos urbanos passa por uma gestão mais eficiente do sistema de **transporte público coletivo**, a implementação de novas tecnologias e a integração de modais como o transporte marítimo.

Nesse cenário, iniciativas como o projeto da Marina da Beira-Mar Norte, que sinaliza o destravamento de um sistema de transporte marítimo, representam um passo positivo. O caminho para uma **mobilidade urbana** mais eficiente exige a colaboração de todos e a implementação de ações concretas para uma cidade mais fluida e conectada.

Convém destacar;

Mobilidade e Transporte Urbano: Panorama 2024

a) A mobilidade urbana em Florianópolis, um dos desafios mais complexos da cidade, apresentou um cenário de contrastes em 2024. Enquanto a capacidade do sistema de transporte público teve um aumento notável, a eficiência e o custo do serviço continuaram a preocupar. A alta motorização da população segue sendo um obstáculo, mas avanços na segurança viária indicam um caminho positivo.

Transporte Público: Custo, Velocidade e Capacidade

b) O custo do transporte público por passageiro subiu para **R$ 5,84** em 2024, continuando a tendência de aumento dos últimos anos. A velocidade média da frota, por sua vez, registrou uma leve queda, chegando a **22,91 km/h**, um índice que a mantém na faixa **amarela** (15-30 km/h) e longe do ideal de fluidez.

c) Em contrapartida, a **capacidade de transporte ofertada** teve um aumento expressivo, atingindo a média mensal de **16.099.959**, superando o pico histórico de 2022. Esse crescimento na oferta é fundamental para atender à crescente demanda. No entanto, o sistema ainda carece de modernização: a frota continua sem veículos movidos a energia elétrica, com **0%** de adoção, e a idade média dos ônibus subiu para **8,94 anos**, indicando que, embora ainda na faixa amarela, a frota está envelhecendo e se distanciando da meta de uma frota mais nova e eficiente.

Desafios da Motorização e Infraestrutura

d) A quantidade de veículos particulares per capita registrou um novo pico, chegando a **0,723**, retornando ao patamar de 2022 e se mantendo muito acima do ideal de 0,3. Esse número elevado de carros é um dos

principais fatores para a baixa velocidade do transporte público e os congestionamentos, que se refletem na velocidade média de viagem durante os horários de pico, que subiu para **21,81 km/h** em 2024. A falta de dados sobre a pavimentação de vias e calçadas também impede uma avaliação completa da infraestrutura de mobilidade a pé e por outros modais.

Segurança e Tendências Positivas

e) No quesito segurança, a cidade manteve o bom desempenho. O número de vítimas mortais em acidentes de trânsito por 100 mil habitantes, embora tenha subido para **8,5** em 2024, permanece na faixa **verde** (<10).

Em resumo, Florianópolis precisa urgentemente equilibrar a oferta crescente de capacidade do transporte público com investimentos na modernização da frota e em infraestrutura. A redução da motorização e o aumento da fluidez do trânsito são desafios que exigem um planejamento abrangente e a implementação de novas tecnologias para transformar o cenário da mobilidade urbana da cidade.

7. 2.4 Tema: Ambiente de Negócios – 01 indicador

a) A análise do **tempo necessário para abrir uma empresa em Florianópolis** mostra um avanço notável e consistente ao longo dos anos. O indicador, que já foi de 15 dias em 2019 e chegou a preocupantes 21 dias em 2020, demonstra agora uma eficiência impressionante. Com o tempo médio caindo para **5 horas em 2024**, a cidade estabelece um novo padrão de agilidade e se consolida na faixa **verde** do sistema de semaforização. Essa redução drástica no tempo de abertura de negócios é um fator crucial para a competitividade de Florianópolis. A agilidade nos processos burocráticos cria um ambiente favorável ao empreendedorismo, atrai novos investimentos e fortalece o ecossistema de inovação, o que é essencial para uma cidade com forte vocação para a economia criativa e tecnológica. Esse desempenho é um sinal claro do compromisso da gestão em remover barreiras e promover o desenvolvimento econômico de forma mais eficiente.

7. 2.5 Tema: Tecido Produtivo – 08 indicadores

a) A análise da movimentação no Aeroporto de Florianópolis para o período de 2022 a 2024 revela uma tendência de crescimento expressiva tanto no transporte de passageiros quanto de cargas. Esse aumento demonstra a crescente relevância do aeroporto como um hub logístico e de turismo para a cidade e a região. **Transporte de Carga:** O volume de cargas transportadas registrou um crescimento notável. A

carga internacional mais que dobrou em dois anos, passando de **2.500 toneladas em 2022** para **6.568 toneladas em 2024**. De forma semelhante, a carga doméstica teve um aumento significativo, indo de **3.550 toneladas em 2022** para **6.578 toneladas em 2024**. Esse desempenho indica um fortalecimento da economia e do comércio da cidade, que está se consolidando como um ponto estratégico para a logística de bens e mercadorias. **Transporte de Passageiros:** O fluxo de passageiros também teve uma ascensão contínua e acentuada. O número de pessoas transportadas aumentou de **3.393.219 em 2022** para quase 5 milhões em 2024, alcançando a marca de **4.895.252 passageiros**. Esse crescimento reflete a recuperação do setor de turismo e a atratividade da cidade, impulsionando a economia local e os serviços relacionados. A disponibilidade de dados nos últimos anos, proporcionada pela concessão do aeroporto, permite um monitoramento contínuo e a criação de uma série histórica confiável. Essa base de informações é fundamental para que o planejamento municipal possa se alinhar à demanda crescente, garantindo a infraestrutura e os serviços necessários para apoiar o desenvolvimento sustentável da cidade.

b) A análise da movimentação na Rodoviária de Florianópolis em 2024 revela uma clara tendência de crescimento e a inclusão de um novo indicador que amplia a capacidade de gestão da cidade. O ano de 2024 marca a primeira coleta de dados sobre o **fluxo de ônibus na rodoviária**(indicador novo). A fonte informou um total de **149.058 viagens** registradas ao longo do ano, sendo 72.618 de chegadas e 76.440 de partidas. A criação deste indicador é um passo importante para um monitoramento mais detalhado da logística de transporte intermunicipal e interestadual, permitindo futuras análises sobre a sazonalidade e a eficiência do serviço. O **número de pessoas transportadas pela rodoviária** demonstra um crescimento contínuo e robusto. O total de passageiros aumentou de **1.642.065 em 2022** para **2.023.555 em 2023**, e em 2024, alcançou a marca de **2.500.536**. Esse crescimento de cerca de 23,6% em relação a 2023 reflete o aumento do turismo e o dinamismo da região. A tendência de crescimento, agora com uma série histórica de três anos, indica que a rodoviária está se consolidando como um ponto cada vez mais vital para a mobilidade de pessoas, exigindo um planejamento que garanta a sua eficiência e capacidade de atendimento.

c) A falta de acesso a dados atualizados pela fonte é o ponto mais crítico na análise do PIB per capita. A repetição do valor de **R$ 45.603** para os anos de **2023 e 2024** demonstra que, desde 2021, a cidade não tem um sistema de monitoramento para um dos indicadores econômicos mais importantes. Essa ausência de dados impede a avaliação do impacto de políticas e do desempenho da economia da capital nos últimos anos. Apesar da falha no monitoramento, uma consulta aos dados oficiais do IBGE, que costumam ter defasagem de dois a três

anos, confirma o potencial econômico de Florianópolis. Segundo o **IBGE**, a cidade manteve uma posição de destaque no ranking nacional de PIB per capita. A última informação consolidada e oficialmente divulgada pelo IBGE é de **2021**. Nela, a capital catarinense registrou um PIB per capita de **R$ 45.603**, o que a colocou em uma posição de liderança entre as capitais brasileiras. O PIB per capita de Florianópolis superou a média nacional e a de diversas outras capitais, evidenciando sua robustez econômica, impulsionada pelos setores de tecnologia, serviços e turismo.

d) A análise da **taxa de crescimento do PIB per capita de Florianópolis** em 2024 revela uma trajetória instável e preocupante nos últimos anos. Após um período de crescimento robusto entre 2019 e 2021, o indicador sofreu uma queda brusca e ainda não se recuperou. Nos anos anteriores, a cidade se destacou por seu desempenho econômico. De 2019 a 2021, a taxa de crescimento se manteve na faixa **verde** (> 2,5%), com picos expressivos, o que a colocou em uma posição de destaque nacional. No entanto, em 2022, a fonte aponta para um crescimento negativo de **-4,46%**, uma retração econômica significativa que interrompeu a tendência de alta. O cenário não melhorou nos anos seguintes, com a taxa de crescimento estagnada em **1,08%** em 2023 e 2024. Esse resultado coloca o indicador na faixa **vermelha** (< 2%), sinalizando que a economia da cidade não está mais superando o crescimento do PIB nacional como em anos anteriores.

7.2.6 Tema: Mercado Laboral – 03 indicadores

A análise dos indicadores de emprego em Florianópolis para 2024 revela um cenário de contrastes que exige atenção. Se, por um lado, a cidade mantém um desempenho robusto no combate ao desemprego, por outro, a composição do mercado de trabalho aponta para desafios na qualidade das ocupações. **A taxa de desemprego de Florianópolis** permanece em um patamar de excelência, situando-se em **4,40%** em 2024. Esse resultado, que a mantém na faixa **verde** (<7%), reflete a força da economia local e sua capacidade de gerar empregos. A estabilidade do indicador, com uma leve variação em relação aos 4,30% de 2023, demonstra uma resiliência notável no mercado de trabalho. Apesar da baixa taxa de desemprego, a análise da **formalidade dos empregos** levanta preocupações. A porcentagem de **população ocupada formalmente** teve uma queda significativa em 2023, para **63,63%**, e se manteve na faixa **vermelha** (<65%) em 2024, com **64,40%**. Esse desempenho é um retrocesso em relação aos 72% de 2022, que colocavam a cidade na faixa amarela. A falta de dados para o indicador de **emprego informal** em 2024 impede uma análise completa, mas a tendência de queda do emprego formal sugere que o baixo desemprego pode estar sendo compensado pelo crescimento do setor informal, onde a proteção e a segurança dos trabalhadores são menores. Para que Florianópolis garanta um desenvolvimento social justo, é fundamental que as

políticas públicas foquem não apenas na criação de empregos, mas na sua formalização e na melhoria de sua qualidade.

7. 2.7 Tema: Educação – 19 indicadores

Educação e Capital Humano

a) A análise dos indicadores de educação em Florianópolis para 2024 revela um cenário complexo, com sinais positivos de inclusão e qualificação docente, mas com preocupantes retrocessos na qualidade da aprendizagem e na estrutura de contratação dos professores.

Qualidade da Aprendizagem e Desempenho (IDEB)

b) Os indicadores de desempenho educacional mostram uma tendência negativa alarmante. A nota do **IDEB** para os anos iniciais caiu de 5,95 (2021-2022) para **5,8** em 2024, mantendo-se na faixa amarela. A situação é ainda mais crítica nos anos finais, onde a nota caiu de 5,2 para **4,6**, saindo da faixa amarela e entrando na **vermelha**. Essa queda nas notas é acompanhada por uma redução drástica no percentual de alunos com desempenho satisfatório. Em Matemática, o índice caiu de 18% para **14%**, e em Leitura, de 43% para **31%** em 2024. Esses dados sinalizam um desafio urgente na qualidade da educação básica do município.

Estrutura e Qualificação do Corpo Docente

c) A estrutura de contratação de professores revela uma tendência preocupante. A porcentagem de **professores efetivos** na rede municipal caiu significativamente, de 51,1% em 2022 para **39,30%** em 2024, entrando na faixa **vermelha**. Em contrapartida, a porcentagem de **contratações temporárias (ACTs)** subiu para **60,7%**, entrando na faixa **vermelha**. Essa precarização do emprego docente pode ser um fator que contribui para a queda na qualidade da aprendizagem.

d) Apesar da instabilidade no modelo de contratação, o corpo docente demonstra alta qualificação. O município alcançou a faixa **verde** em especialização, com **61,07%** dos professores, e em mestrado (**13,12%**) e doutorado (**4,17%**), o que os coloca nas faixas amarela e verde, respectivamente. Isso evidencia um capital humano qualificado que, no entanto, opera em uma estrutura de trabalho cada vez mais instável.

Inclusão e Acessibilidade

e) Nos indicadores de inclusão, Florianópolis mostra um desempenho positivo e consistente. O número de estudantes com necessidades especiais matriculados na educação básica continuou a crescer, chegando a **1.952 alunos** em 2024. Além disso, a acessibilidade nas escolas foi mantida em um patamar de excelência, com **96,21%** das

unidades de ensino cumprindo a Lei de Acessibilidade, o que mantém a cidade na faixa **verde** e demonstra um forte compromisso com a inclusão.

Alfabetização e Nível Superior

f) A taxa de analfabetismo, que havia caído para 1,10% em 2023, voltou a subir para **1,4%** em 2024, mantendo o indicador na faixa **amarela**. A falta de dados atualizados sobre o número de pessoas com ensino superior completo (>25 anos) impede uma análise precisa do capital humano da cidade, uma vez que o dado de **383.891** pessoas está estagnado desde 2022.

Em suma, Florianópolis tem feito avanços importantes em inclusão e qualificação docente, mas os dados de 2024 sobre o desempenho educacional e a precarização do corpo docente são sinais de alerta que precisam de atenção imediata para que a cidade não comprometa o seu futuro capital humano.

7. 2.8 Tema: Segurança – 10 indicadores

A análise dos indicadores de segurança pública em Florianópolis para 2024 revela uma tendência geral positiva, com a cidade mantendo um desempenho sólido na redução de crimes violentos e contra o patrimônio. Apesar de oscilações, a capital consolida-se em um patamar de segurança elevado quando comparada a outras cidades brasileiras.

Crimes Violentos: Tendência de Baixa Continua

a) A taxa de **homicídios por 100 mil habitantes** permaneceu na faixa **verde** (<10), registrando **5,40** em 2024. Embora represente uma leve alta em relação aos 4,50 de 2023, o valor demonstra que a tendência de queda gradual observada desde 2019 se mantém, afastando a cidade da faixa amarela e vermelha. Da mesma forma, os **latrocínios** registraram um resultado excelente em 2024, com **0,00** por 100 mil habitantes, mantendo-se na faixa verde.

b) O número de **feminicídios** por 100 mil mulheres teve uma leve alta em 2024, chegando a **0,50**, o que mantém a cidade na faixa **verde** e abaixo dos picos de anos anteriores.

Crimes contra o Patrimônio: Estabilidade e Oscilações

c) Os crimes contra o patrimônio, em sua maioria, também se mantiveram em patamares controlados. Os **roubos** por 100 mil habitantes registraram **153** em 2024, mantendo a cidade na faixa **verde** (<300). De forma similar, os **roubos de veículos** por 100 mil habitantes caíram para **13,9**, um dos menores índices da série histórica.

d) Os **furtos** e os **crimes contra a propriedade** apresentaram uma situação mais volátil. Embora os furtos tenham registrado um leve recuo em 2024 (2661,4), o número permanece em patamares elevados. Já os crimes contra a propriedade recuaram de 10,9 em 2023 para **8,8** em 2024, mantendo-se na faixa verde.

Em resumo, os dados de 2024 reforçam a percepção de que Florianópolis é uma cidade segura, especialmente em relação a crimes violentos. A manutenção da taxa de homicídios e a queda nos roubos e roubos de veículos são destaques positivos. No entanto, é necessário manter o monitoramento e o investimento em prevenção para evitar a escalada de furtos e garantir que a segurança continue a ser uma prioridade.

7. 2.9 Tema: Saúde – 43 indicadores

Mortalidade e Saúde da População

a) A cidade demonstra uma tendência positiva na redução das taxas de mortalidade. A **Taxa de Mortalidade Geral** continuou a cair em 2024, chegando a **518,60 por 100 mil habitantes**. Essa redução é observada tanto em homens (548,67) quanto em mulheres (490,40), indicando uma melhora geral na expectativa de vida.

b) A taxa de **mortalidade infantil** se manteve consistentemente na faixa **verde** (<20), variando de **5,22 em 2019** a **6,90 em 2024**. Essa estabilidade em um patamar baixo é um sinal claro da qualidade dos cuidados com a saúde de crianças na cidade. A mortalidade por **causas externas** teve um pico em **2022 (50,82)**, mas apresentou queda para **44,59 em 2024**, mostrando progresso. A **Taxa de Mortalidade por Doenças Cardiovasculares** também recuou em 2024 para **141,40**, após um pico em 2023. No entanto, a **Taxa de Mortalidade por Neoplasias** (câncer) teve uma leve redução, mas permanece em um patamar elevado, de **140,19**, indicando a necessidade de maior atenção a essa área.

Infraestrutura e Serviços de Saúde

c) A infraestrutura de saúde da cidade continua robusta. A **Quantidade de Leitos de Hospital** por 100 mil habitantes registrou **347,02** em 2024, mantendo-se na faixa **verde** (>100) e bem acima da meta ideal. De forma similar, a **Quantidade de Médicos** por 100 mil habitantes chegou a **3.060,03** em 2024, um número impressionante que mantém a cidade na faixa **verde** (>200) e demonstra a alta disponibilidade de profissionais de saúde. A cobertura da saúde da família também é um ponto forte. Após um salto em **2021 (108,88%)**, o índice se estabilizou em um patamar acima de 100%, chegando a **108,39%** em 2024.

Doenças Crônicas e Cobertura Vacinal

d) O monitoramento da prevalência de doenças crônicas apresenta uma lacuna crítica. Os dados de 2024 para a **Prevalência de Hipertensão e Diabetes** não foram fornecidos, impossibilitando uma avaliação da evolução dessas condições que, nos anos anteriores, já se encontravam em uma situação preocupante. A **Prevalência de Obesidade** teve um pequeno aumento para **21,91%** em 2023.

e) A maioria das vacinas teve um aumento significativo na cobertura entre 2023 e 2024, o que é uma tendência muito positiva. As coberturas para **Pentavalente, Pneumo 10, Poliomielite e Tríplice Viral** mostram avanços de mais de 5% em um único ano. A **DTPA ADULTO** alcançou **75,39%**, aproximando-se da meta. Apesar do progresso, muitas vacinas permanecem com baixa cobertura e longe das metas. A BCG (**39,17%**) e a Hepatite B ao nascer (**34,94%**) continuam na faixa **vermelha**, indicando uma falha na imunização nos primeiros meses de vida. A cobertura da **Varicela** (**56,70%**) e da **Febre Amarela** (**66,39%**) também está muito abaixo da meta de 95%.

A análise da saúde em Florianópolis em 2024 reforça a percepção de que a cidade possui um sistema de saúde com infraestrutura e profissionais de alto nível, o que se reflete na baixa mortalidade. No entanto, a ausência de dados cruciais sobre doenças crônicas e a baixa cobertura de algumas vacinas indicam a necessidade de um sistema de monitoramento mais abrangente. Para uma visão completa, é fundamental que a cidade vá além do registro de doenças e invista na coleta de indicadores de **saúde da população**, promovendo uma abordagem mais preventiva e proativa.

7. 2.10 Tema: Capital Humano – 02 indicadores:

Os investimentos em cultura em Florianópolis demonstram uma clara e consistente elevação de prioridade nos últimos anos, refletindo um compromisso em fortalecer o capital humano da cidade. A análise dos dados de 2024 confirma que a cidade se consolidou em um patamar de destaque nesse quesito.

Investimento per capita em Cultura

a) Após uma queda em 2020 e 2021, o investimento em cultura por habitante teve uma recuperação notável. Em **2022**, o valor de **R$ 26,24** já posicionava a cidade na faixa amarela. O ano de **2023** marcou uma mudança de patamar, com o investimento saltando para **R$ 58,22**, o que coloca a cidade na faixa **verde** de excelência. Em **2024**, o valor se manteve em um nível elevado, registrando **R$ 52,26**. Essa consistência mostra que a priorização da cultura não foi um evento isolado, mas uma decisão estratégica para a cidade.

Investimento em Cultura sobre Receita Corrente Líquida

b) O indicador que mede o investimento em relação à receita da prefeitura também ilustra essa nova prioridade. Depois de anos com percentuais abaixo de 1% , o investimento atingiu **1,04%** em 2023, representando um novo patamar de comprometimento. Embora o percentual tenha recuado para **0,89%** em 2024, a análise da série histórica mostra que a cidade elevou o peso da cultura em seu orçamento, saindo de uma posição de desvantagem para uma de maior prioridade.

Em suma, os dados de 2024 confirmam uma tendência muito positiva. Florianópolis não apenas se recuperou dos baixos investimentos de anos anteriores, mas estabeleceu um novo padrão de alocação de recursos para a cultura, alinhando-se à sua identidade de cidade criativa e tecnológica e reforçando um dos pilares de seu capital humano.

7. 2.11 Tema: Tecido Empresarial – 15 indicadores

Com base nos 15 novos indicadores, que, embora ainda sem semaforização, já oferecem uma base histórica para análise, é possível traçar um panorama promissor e dinâmico do tecido empresarial de Florianópolis. Os dados desde 2019 revelam uma economia em crescimento, com resiliência pós-pandemia e setores estratégicos em ascensão.

Crescimento Geral e Dinamismo

a) O cenário empresarial de Florianópolis demonstra um dinamismo notável. O **número de empresas** ativas na cidade teve um aumento expressivo, passando de **7.660 em 2021** para **24.779 em 2024**. Esse crescimento exponencial, combinado com uma taxa anual de abertura de novas empresas consistentemente acima de 20%, indica um ambiente favorável ao empreendedorismo e uma economia vibrante.
b) O **percentual de exportações** de bens e serviços também reforça essa tendência, com um aumento contínuo. O valor das exportações cresceu de **US$ 40,84 milhões em 2021** para **US$ 65,23 milhões em 2024**, sinalizando uma crescente inserção da cidade no comércio internacional.

Desempenho dos Setores Chave

c) **Tecnologia:** O setor de tecnologia consolida sua posição como motor da economia local. O crescimento de pessoas empregadas manteve-se forte, e o faturamento das empresas teve um aumento de **28,39%** em 2024, após uma alta de 25,07% no ano anterior. A participação do setor na arrecadação de impostos totais cresceu de **15,78% em 2023** para **18,87%** em 2024, demonstrando sua relevância fiscal e econômica.
d) **Turismo e Gastronomia:** O setor de hotelaria, bares e restaurantes mostrou uma recuperação robusta após os impactos da pandemia. A **ocupação de leitos** em hotéis e pousadas alcançou **63,80%** em 2024, superando os 57,16% de 2023. O faturamento de bares e

restaurantes teve um crescimento sólido de **13,04%** em 2024, e sua participação na arrecadação de impostos totais dobrou em um ano, chegando a **2,14%**, um sinal de recuperação e formalização.

e) **Saúde Privada:** O setor de saúde privada também se destaca, com um crescimento constante em sua participação nos impostos, que chegou a **6,32%** em 2024. Isso reflete o papel crescente do setor na economia e na prestação de serviços à população.

A análise dos indicadores mostra que o tecido empresarial de Florianópolis é resiliente e dinâmico. Os dados de 2024 reforçam a importância dos setores de tecnologia, turismo e saúde para o desenvolvimento da cidade. A tendência geral de crescimento no número de empresas, nas exportações e no faturamento dos setores-chave é um sinal muito positivo. No entanto, a falta de dados sobre o crescimento de empregos em setores como hotelaria e bares e restaurantes é uma lacuna a ser superada, sendo essencial para uma análise completa do mercado de trabalho.

7. 3 - Dimensão Fiscal e Governança

7.3.1 Tema : Gestão Pública Participativa – 01 indicador

A análise do único indicador para o tema de Gestão Pública Participativa revela uma inconsistência fundamental, que impede o monitoramento efetivo do envolvimento da sociedade civil na definição do orçamento. A ausência de uma métrica clara e consistente ao longo dos anos torna impossível avaliar a evolução da participação popular.

O **indicador de porcentagem do orçamento com participação da Sociedade Civil** passou por uma série de mudanças em sua medição. O ano de 2019 apresentou um valor de 12,47%, mas a partir de 2020, a métrica mudou para 5% da arrecadação do IPTU, um valor que, embora fixo, representa uma porção muito limitada do orçamento municipal.

A falta de uma métrica quantitativa se acentuou ainda mais em 2024, quando o indicador passou a ser descrito como um processo legal de pelo menos duas audiências públicas para cada peça orçamentária (PPA, LDO e LOA). Embora a realização de audiências seja um avanço em termos de processo e formalidade, a mudança impede que se meça a porcentagem real do orçamento influenciada pela população.

7. 3.2 Tema: Gestão Pública Moderna – 09 indicadores

a) A gestão municipal avança de forma notável na modernização de seus processos. Em 2024, a porcentagem de **processos digitais concluídos** alcançou **88%**, colocando a cidade na faixa amarela e a um passo de alcançar o patamar de excelência. Esse resultado reflete o sucesso na digitalização e na agilidade dos serviços.

b) O compromisso com a transparência também é evidente. O **Índice de Transparência da Gestão Municipal** se manteve em **98%** em 2024, na faixa verde, enquanto o número de **serviços online para o cidadão** cresceu de forma constante, chegando a **210** e colocando a cidade na faixa verde por oferecer mais de 200 serviços.

Compras Públicas: Modernização e Desafios

c) A Prefeitura de Florianópolis fez um progresso significativo na modernização de suas compras. As modalidades de **pregão presencial e tomada de preços** foram praticamente eliminadas, ambas com **0%** de participação em 2024. Em contrapartida, o **pregão eletrônico** representou **53,62%** do total das compras.

d) No entanto, um ponto de preocupação é o crescimento expressivo das compras por **contratação direta**, que subiram de **2,27% em 2020** para **20,55% em 2024**. Esse aumento no uso de compras sem licitação representa um retrocesso em relação à transparência e à competitividade, exigindo um rigoroso monitoramento por parte da gestão municipal.

Eficiência da Gestão de Pessoal

e) A análise dos gastos com pessoal e da eficiência demonstra desafios a serem superados. Em 2024, a porcentagem de **gasto com pessoal** em relação ao gasto total foi de **46,07%**, uma redução de 15,5% em comparação com o ano anterior. Apesar dessa melhora, a eficiência pode ser comprometida pelo alto índice de **horas de falta**, que somou **10,76%** em 2024. Esse percentual corresponde a mais de um mês de trabalho perdido por ano.

Em resumo, a cidade de Florianópolis se destaca como líder em modernização digital, com indicadores de serviços online e transparência em patamares de excelência. No entanto, a gestão enfrenta uma contradição: o avanço tecnológico em serviços não foi acompanhado pela melhoria em processos fundamentais de gestão fiscal, transparência em compras e eficiência de pessoal, o que exige atenção urgente para garantir um desenvolvimento completo e sustentável.

7.3.3. Tema: Transparência -01 indicador

a) Pelo portal https://radardatransparencia.atricon.org.br/, observamos que Florianópolis, desde o ano de 2022, apresenta uma classificação ouro, numa média de 89,44%, considerada excelente.

7. 3.4 Tema: Impostos e Autonomia Financeira - 11 indicadores

a) Os indicadores deste grupo estão razoavelmente adequados com as seguintes exceções:
   i) Indicador "**Porcentagem da variação anual da cota parte do ICMS**" e "**Porcentagem de variação anual da arrecadação do ISS**"- Indicam que a atividade econômica tem crescimentos pois: "% de variação do ICMS e do ISS" foi superior ao IPCA de 2024 (4,83). O ICMS cresceu 7,8 acima do IPCA e do ISS 5,1% acima do IPC``
   ii) O Indicador "**Porcentagem de variação anual da arrecadação do IPTU**" foi de 2,09% (abaixo da inflação), o que indica deficiência da administração no processo de cobrança ativa e/ou valores da planta de imóveis não atualizadas.
   iii) Indicador "**Porcentagem de variação da dívida ativa"** - nos mostra um crescimento contínuo, desde 2020, o que indica uma grande dificuldade da administração de cobrar os seus devedores.
   iv) Indicador "**Porcentagem de inadimplência do IPTU**"- Este indicador teve uma redução em relação aos 2 anos anteriores, mas ainda assim é elevado 16,7%.

7. 3.5. Tema : Gestão do Gasto Público – 05 indicadores

a) Indicador "**Porcentagem dos gastos correntes em relação aos gastos totais**" - Em 2024 foi levemente inferior ao IPCA, apresentando o resultado de 86,21%, o que é bastante positivo, mas quase não existe sobra de recursos para investimentos na obras necessárias para o desenvolvimento da cidade, o que está na origem do crescente endividamento da cidade, que tem brecado o acesso a mais créditos no sistema financeiro.
b) Para o indicador "**Taxa de crescimento anual do gasto corrente**": Com base na adequação de dados apresentada pela fonte, verificamos que o Indicador cresceu em torno de 106% no intervalo 2017 a 2024, enquanto o IPCA no período subiu 48,6%, ou seja um crescimento real acima de 40%. No ano de 2024 esta despesa cresceu 4,46% ficando levemente abaixo do IPCA do ano. Isto é bastante positivo, mas deveria ser acelerada esta redução da despesa para melhorar a capacidade de investimento e possibilitar a redução do endividamento que é extremamente elevado.

7. 3.6 Tema : Gestão da Dívida – 04 indicadores

a) Indicador "**Despesas de Pessoal em relação a receita líquida**" - Este indicador em 2024 apresentou o resultado de 48,46% e está levemente abaixo do ano anterior, mas já esteve em 45% nos anos 2021/2022.

b) Indicador "**Despesas com terceirização de pessoal (PJ + PF + Locação de Mão de obra)**" - Indicador foi 4,2% em 2024 e mantem-se na faixa dos anos anteriores. Devemos observar que este indicador somado ao indicador "**Despesa de pessoal/Receita corrente líquida: percentual da despesas totais (salário + encargos + vales transporte e alimentação + plano de saúde) e de pessoal em relação a receita corrente líquida**" resulta num custo de pessoal total de praticamente 53% da receita líquida.

c) Independemente dos Indicadores de Custo de Pessoal (200 e 201) estarem ou não dentro dos limites legais, consideramos elevado um gasto de 53% da Receita Líquida com Pessoal. Devemos lembrar que existem os demais gastos gerais para fazer a máquina funcionar. A prioridade deveria ser reduzir esta despesa para que fosse possível bancar os investimentos que a cidade precisa para melhorar a qualidade de vida e reduzir o endividamento que hoje dificulta o acesso a crédito.

d) Indicador "**Crescimento da dívida: Porcentagem de crescimento da dívida (Empréstimos de curto e longo prazo)**" - Em 2024 foi apresentado um crescimento da dúvida, passando de -4,91 (2023) para 16,94% o chama atenção.

e) Indicador "**Dívida consolidada líquida/Receita corrente líquida: Porcentagem da dívida consolidada líquida em relação a receita corrente líquida**" - Apresentou o índice de 34,75% em 2024 considerado satisfatório.

8. CONSIDERAÇÕES FINAIS

Nesta 9ª edição do Relatório dos Indicadores de Sustentabilidade de Florianópolis (RAPI), o panorama geral reflete uma cidade de contrastes, com avanços notáveis em alguns setores, mas com desafios persistentes em áreas-chave para a sua sustentabilidade. Embora o relatório aponte melhorias em certos indicadores, a análise de 2024 revela que as preocupações dos relatórios anteriores ainda não se traduziram em avanços significativos em diversos temas.

Uma das maiores contradições se manifesta na **Gestão Pública e Transparência**. A cidade se consolida como líder em governo digital, com um alto percentual de processos concluídos de forma eletrônica e um índice de transparência em patamares de excelência. No entanto, a transparência ainda deixa a desejar em aspectos fundamentais. É difícil para a sociedade fiscalizar os processos licitatórios de obras públicas, pois os portais não disponibilizam os documentos de forma tempestiva. Essa falha no acompanhamento se reflete na plataforma "Floripa em Números", que carece de atualizações, com dados desatualizados em relação aos fornecidos pelas diversas fontes municipais.

No **Meio Ambiente**, o cenário é misto. O crescimento da malha urbana tem sido mantido em um ritmo saudável e planejado, mas a cidade continua a enfrentar problemas estruturais graves. O consumo de água per capita

permanece acima das recomendações internacionais, as perdas por água não contabilizada se mantêm em níveis críticos, e a porcentagem de moradias afetadas por inundações cresce de forma preocupante. A gestão de resíduos, por sua vez, mostra uma tendência positiva na compostagem, mas o avanço é lento em comparação com o alto nível de resíduos destinados a aterros sanitários e a ausência total de iniciativas para geração de energia a partir de lixo. A falta de monitoramento em indicadores estratégicos, como o saldo hídrico e a ocupação em áreas de risco, agrava o quadro. A questão do saneamento básico continua a ser um dos maiores desafios, com o índice de cobertura de esgotamento sanitário ainda muito abaixo do necessário. O sistema de drenagem insuficiente reflete investimentos estruturais que não têm acompanhado o crescimento da cidade.

Do ponto de vista **econômico**, a cidade demonstra resiliência. O PIB per capita a coloca em uma posição de liderança nacional, e a economia se mostra dinâmica, com forte crescimento em setores-chave como tecnologia e turismo. O mercado de trabalho mantém uma baixa taxa de desemprego. No entanto, o crescimento do PIB per capita tem sido volátil nos últimos anos e a qualidade dos empregos gera preocupação, com a porcentagem de empregos formais em queda.

Por fim, no aspecto **fiscal**, o relatório aponta grandes preocupações. Há quase nenhuma sobra de recursos para investimentos em obras estruturantes, o que está na origem do crescente endividamento da cidade. O aumento da dívida já dificulta o acesso a financiamentos para projetos essenciais, especialmente aqueles ligados à mobilidade. O alto gasto com pessoal, que consome uma fatia significativa da receita, também representa um desafio para a gestão.

É importante registrar que solicitamos às fontes, a revisão dos indicadores desde o ano de 2020 para confirmação das informações, eventuais ajustes ou complementos. Portanto, os indicadores e as semaforizações de 2020 a 2023 registrados nesse relatório, podem ter sofrido alterações em comparação aos relatórios anteriores.

O Relatório dos Indicadores de Sustentabilidade de Florianópolis (RAPI), em sua 9ª edição, pretende ser um instrumento para avaliar as políticas públicas urbanas e as diretrizes da AGENDA FLORIPA 2030/40/50.

A análise deste ano reforça a necessidade da cidade resolver suas lacunas de dados e de traduzir o sucesso em digitalização e economia em uma gestão fiscal e ambiental mais sólida. O desafio para o futuro é grande, mas as informações do relatório fornecem o caminho para que Florianópolis se torne uma sociedade verdadeiramente inclusiva, sustentável e equitativa.

9. AGRADECIMENTOS:

Agradecemos ao Prefeito de Florianópolis, Topázio Neto, seus secretários municipais, gestores e servidores da administração pública, bem como secretarias estaduais, empresas públicas e autarquias por seus esforços e contribuições no fornecimento dos dados solicitados.

Fontes diretamente envolvidas no fornecimento dos indicadores as quais agradecemos:

Acate - Associação Catarinense de Tecnologia
ACM - Associação Catarinense de Medicina
Casan - Companhia Catarinense de Águas e Saneamento
Celesc - Centrais Elétricas de Santa Catarina S.A
Comcap - Companhia Melhoramentos da Capital
Cosip - Contribuição de Serviço de Iluminação Pública
Defesa Civil de Florianópolis
Floram - Fundação Municipal do Meio Ambiente de Florianópolis
Floripa Airport
Ipuf - Instituto de Pesquisa e Planejamento Urbano de Florianópolis
REPLAN - Portal Rede de Planejamento - https://redeplanejamento.pmf.sc.gov.br/pt-BR/indicadores/lista
SC Gás - Companhia de Gás de Santa Catarina
Secretaria de Estado de Segurança Pública
Secretaria Municipal de Administração
Secretaria Municipal de Assistência Social
Secretaria Municipal de Cultura, Esporte e Lazer
Secretaria Municipal de Educação
Secretaria Municipal de Fazenda
Secretaria Municipal de Infraestrutura e Manutenção da Cidade
Secretaria Municipal de Licitações, Contratos e Parcerias
Secretaria Municipal de Meio Ambiente e Desenvolvimento Sustentável
Secretaria Municipal de Planejamento, Habitação e Desenvolvimento Urbano
Secretaria Municipal de Saúde
Secretaria Municipal de Segurança e Ordem Pública
Secretaria Municipal de Turismo, Desenvolvimento Econômico e Inovação
SHRBS - Sindicato de Hotéis, Restaurantes, Bares e Similares de Florianópolis

Também, agradecemos imensamente ao incansável Grupo de Trabalho do RAPI, composto por membros da Associação FloripAmanhã, do Grupo Estratégico de Inteligência da Universidade Federal de Santa Catarina (UFSC) e os membros do Observatório Social do Brasil – Florianópolis, que atuaram na revisão dos indicadores, no acompanhamento, na coleta, análise dos dados recebidos, e na elaboração do presente relatório.

Vamos, juntos, fazer uma cidade mais sustentável!



RAPI 2024-2025 RELATÓRIO ANUAL DE PROGRESSO DOS INDICADORES

Grupo de Trabalho de Indicadores

Associação FloripAmanhã
Andrea Pessi M Costa
Ivo Sostizzo
Márcia Regina Teschner
Pedro Carlos Rasia
Salomão Mattos Sobrinho

Observatório Social do Brasil - Florianópolis
João Manuel Dias da Silva
Rafael Novaes

Universidade Federal de Santa Catarina
Clarissa Stefani Teixeira
Hans Michael Van Bellen

É permitida a reprodução parcial ou total deste material desde que citada a fonte Rede Ver a Cidade Floripa, 2024-2025.

Outubro de 2025